17/02/2026

בדיקת התכנות משפחת חסון מושב כפר בן נון

מטרות בדיקת ההתכנות:

- יצירת מתווה הסדרה למשק
- הערכת עלויות חריגות והסדרה
- תחשיבים להיוון 3.75%
- מתווה להקמת בית מגורים שלישי
- מתווה להקמת פל"ח

בדיקת ההתכנות התחלקה למספר שלבים:

1. סקירת החומרים וקבלת סטטוס עדכני- סריקת מפת מדידה שהתקבלה, סריקה של כלל ההיתרים, סקירת התב"ע הקיימת ותבע"ות אחרות רלוונטיות, השוואת ההיתרים למצב הקיים ואיתור חריגות.

2. הקמת מתווה הסדרה למשק – תחשיבי הערכת עלויות הגשה במצב קיים, ופתרונות הסדרה לקיים במשק.

3. ביצוע תחשיבי פיתוח – עלויות רכישת זכויות מהוונות 3.75% או 33%, עלויות דמי היתר למגורים, תחשיבי פל"ח ותחשיבי פיצול.

4. יצירת מתווה תכנוני – על פי המצב הקיים בנחלה, בהתאמה למפת המדידה הנוכחית והתוכנית העתידית למשק.

שווי הזכויות בנחלה הסתמך על נתונים וסריקת שומות בסביבה משנים 2024 - 2025. בדיקת ההתכנות בוצעה על סמך גבולות התב"ע הנוכחית. **דמי ההיתר והנחיות רמ"י שבבדיקה הינם בהתאם למועד הבדיקה ויכולים להשתנות והינם מתעדכנים בהתאם למועד הגשת הבקשה לרמ"י.**

מזמין העבודה מודע לכך שלא בוצעה שומה למשק, ושהערכות אלו בוצעו לשם קבלת סדר גודל ראשוני בלבד ואינם מהוות אסמכתא משפטית.
בדיקת ההתכנות לא כוללת בתוכה חישובי אגרות בניה מיסים והיטלים.

העבודה בוצעה על פי מפת מדידה מצבית שסיפק מזמין הבדיקה ולבקשתו מיום 30/08/2023 ע"פ תב"ע 426-0218065 אשר מציינת את שטחי המבנים וגבולותיהם החיצוניים בלבד ועל כן קיימת מגבלה לבחינת המצב הבנוי הפנימי של המבנים, גבהים וחזיתות.

בדיקת התכנות זו הוכנה עבור מזמינה ולמטרתה בלבד. אין היא מהווה תחליף לייעוץ משפטי ו/או לשומה שנערכה על ידי שמאי מקרקעין מוסמך ואין להסתמך עליה לכל מטרה אחרת. השימוש בה נאסר על כל צד שלישי שהוא אינו המזמין, ועורכי בדיקת ההתכנות לא יהיו אחראים להסתמכות כלשהי כאמור. מובהר, כי בדיקה זו אינה מהווה תחליף לייעוץ מקצועי.

ניתוח תב"ע קיימת

על המושב חלה תב"ע 426-0218065. עיקרי זכויות התב"עות הנוכחיות הם:

- הקמת 3 בתי מגורים 620 מ"ר עיקרי + 180 מ"ר שירות
- יחידה צמודת קיר 55 מ"ר
- בריכת שחייה
- מגורי עובדים זמניים בחלקת המגורים

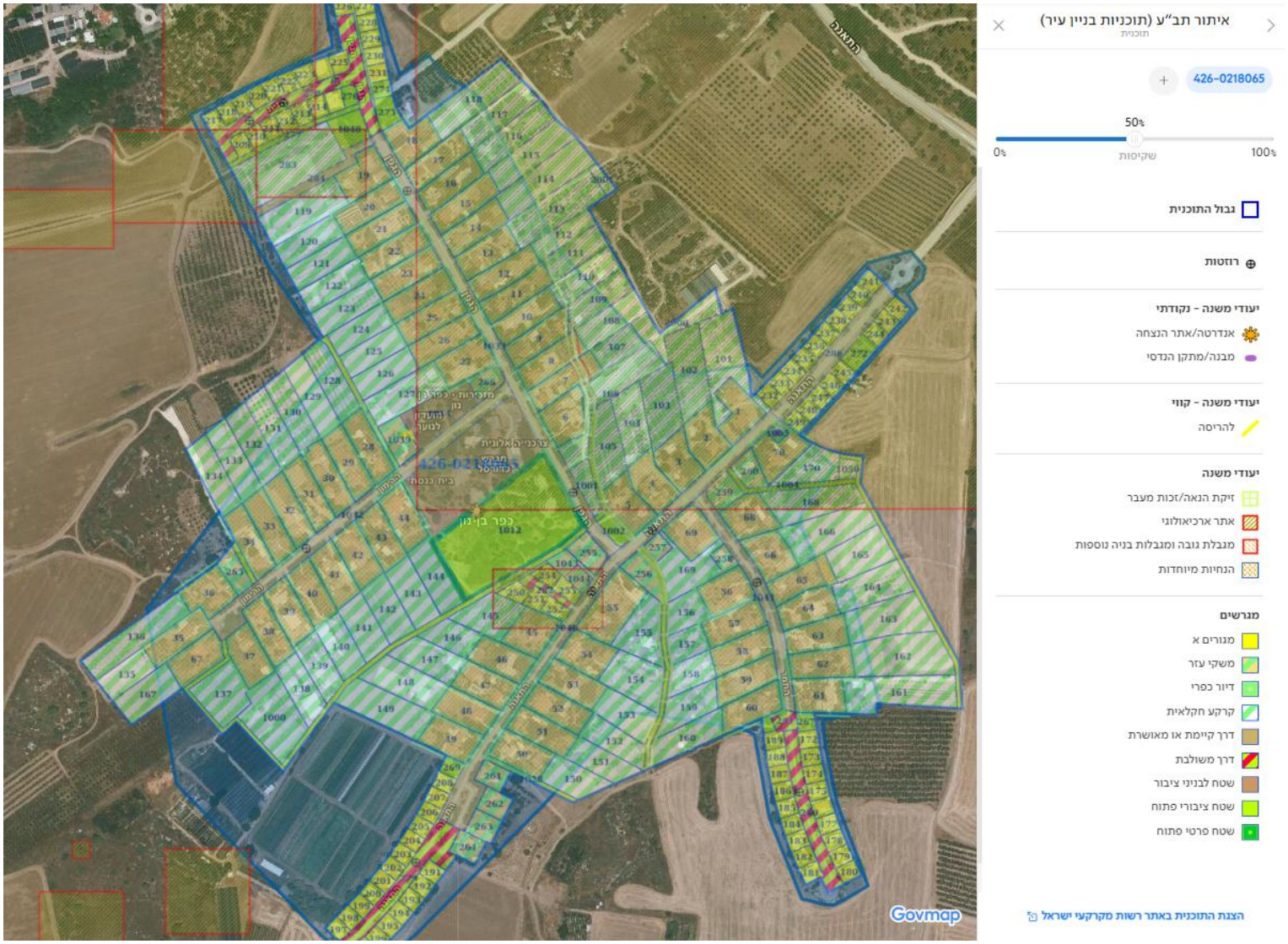

תב"ע לפל"ח

בהתאם לגז/1000 להלן השימושים המותרים במסגרת פל"ח, בנוסף לתב"ע המושבית המוצגת מעלה.

פרק ג'–השמושים המותרים למטרות פל"ח בחלקה א'

19. **להלן שימושי פל"ח שיותרו בהתאם להוראות תכנית זו:**

א. אחסנה למעט אחסנה גלויה ולמעט איחסון של חומרי הדברה, (פרט לחומרי הדברה ואיחסון גלוי הדרושים במשרין לשימוש החקלאי הפרטי של בעל הנחלה לעיבוד נחלתו בלבד), חומרי ניקוי ופעולות אריזה ומילוי חומרים אלה, וכן למעט איחסון פסולת, גרוטאות וחומרי בנין משומשים.

ב. מלאכה ותעשיה זעירה.

ג. תעשיה חקלאית זעירה.

ד. שירותי משרד שונים לבעלי מקצועות חופשיים, פעוטונים, גני ילדים.

ה. מבני מגורים לפועלים זמניים בחקלאות.

ו. מבנה קייט כפרי.

סוג השמוש	מספר יח' בנחלה	סה"כ השטח לבניה (עיקרי + שירות) בשטח המותר	גובה מירבי/ מס' קומות	קווי בנין	מרווחים		
מבני פל"ח לשימושים כאמור בפרק ג' סעיף 19 (א'-ג')	_____	עד 500 מ"ר	עד 5.2 מ' גובה שיא הגג מפני הקרקע	לפי תוכנית מתאר/מפורטת החלה במקום	מרחק בין מבנה פל"ח לכל מבנה אחר בנחלה עד 0 מ'	מרחק בין מבנה פל"ח לכל מבנה מגורים בנחלה גובלת מינ' 25 מ'	מרחק בין מבנה פל"ח לבין כל מבנה שאיננו למגורים בנחלה גובלת מינ' 8 מ'
מבני פל"ח לשימושים כאמור בפרק ג' סעיף 19 (ד')	_____	עד 100 מ"ר (ששטח זה יופחת משטחי בניה מותרים לשטחי פל"ח)	עד גובה 3.4מ' גג שטוח	לפי תוכנית מתאר/מפורטת החלה במקום	_____		
מבני מגורים לפועלים זמניים בחקלאות כאמור בפרק ג' סעיף 19 (ה')	מבנה אחד בנחלה	לא יעלה על- 45 מ"ר ולא יקטן מ- 25 מ"ר	3.5 מ' קומה אחת	לפי תוכנית מתאר/מפורטת החלה במקום	מרחק בין מבנה מגורים למבנה לפועלים זמניים מינ' 5מ'		
מבנים לאירוח כפרי כאמור בפרק ג' סעיף 19 (ו')	2 יח' לכל דונם מתחום המגורים, ולא יותר מ-4 יח'	לא יעלה על- 40 מ"ר ולא יקטן מ- 25 מ"ר ליח"ד אחת (שטח זה יופחת משטחי בניה מותרים לשטחי פל"ח)	3.5 מ' קומה אחת	ק: 5 מ' צ: 4 מ' א: 6 מ'	מרחק בין מבנה מגורים למבנה קייט מינ' 10מ' (לא תותר הקמת מבנים לקייט בצמוד למבנה המגורים)		
סה"כ כל השימושים	500 מ"ר						

היוון המשק

כיום, בעל הנחלה כ"בר-רשות" זכאי לבניה של שתי בתי מגורים בגודל 160 כ"א + יחידה להורים בגודל 55 מ"ר, סה"כ 375 מ"ר, במידה ובעל המשק רכש מטרים נוספים בעבר לטובת הבתים הקיימים בנחלה הם יתווספו לסל הזכויות. על זכויות אלו חלות דרישה רצף בין דורי ומעמדו בזכויות אלו הוא כבר-רשות. רמ"י מאפשרים לבעל הנחלה לעגן ולרכוש את זכויות במשק ובעצם לעבור מבר-רשות למעמד של חוכר בנחלה שלו. ההיוון מתבצע על חלקת המגורים בהתאם לתב"ע הקיימת עד מגבלת 2.5 דונם. בהתאם לכך מוצעים שני מסלולי כניסה להסדר:

מסלול דמי חכירה – 3.75%

במסלול זה, בעל הנחלה רוכש ומעגן את זכויותיו הבסיסיות שהוענקו לו עם קבלת הנחלה. כלומר לא נוצרות זכויות חדשות מעבר לקיים, אך נוצרות יותר אפשרויות לבעל הנחלה עם אותן זכויות. אז מה נקבל במסלול זה?

-כאשר ניכנס למסלול זה בעל הנחלה רוכש את זכויות הבניה הבסיסיות שקיבל, כך שהוא יכול להשתמש **ב375** מ"ר כרצונו ולייעד אותן בין היחידות השונות. לדוגמא, בנית יח"ד אחת בגודל 375 מ"ר **ללא תשלום דמי היתר**.

-בנוסף, בעל הנחלה מקבל **פטור** מהדרישה לרצף בין דורי בנחלה.

- לאחר כניסה למסלול ההיוון ניתן להקים בית שלישי בנחלה (לא ניתן לעשות ללא היוון)

- לאחר הכניסה להסדר יכול בעל המשק לבצע פיצול נחלה, בהשלמה ל-33% משווי **המגרש המפוצל**, כאשר ללא כניסה להסדר הדבר לא אפשרי.

- בעל הנחלה הופך לחוכר וחותם על חוזה חכירה עם הזכויות שפורטו מעלה.

עלות מוערכת של דמי החכירה בכניסה להסדר: כ- 340,000 ₪
יש להוסיף תשלום מס רכישה כחוק.

סטטוס היתרים בנחלה

מבדיקה שנערכה מול הוועדה המקומית לתכנון ובניה "גזר", נמצא כי בתיק הבניין של הנחלה קיימים רק טפסי היתר מילוליים ללא תכניות היתר המגדירות מיקום ו/או צורה של מבנים.

הוועדה נשאלה על ידינו האם תכיר במבנים המצויים בנחלה כמבנים בהיתר, תשובת הוועדה היא כי מבחינתם קיימים היתרים למבנים במשק מאחר ויש טפסי היתר חתומים, אך יש לבדוק התאמה של המבנים לטפסי ההיתרים הנ"ל ע"פ השטחים ותיאור הבקשה המופיעים בהם.

בבדיקת ההתכנות התייחסנו לגדול המבנים בפועל בהשוואה לגודל המבנים בטפסי ההיתר ולתיאור הבקשה ובהתאם לכך ניתנה אבחנה לכל מבנה.

מצורף בזאת תשובות הוועדה המקומית בנושא.

ספיר אלקובי <sapirn@Gezer-region.muni.il>
אל Roi Boost

הי',
לצערי אין לנו בוועדה את התיעוד של הגרמושקות.
– תנסו לבדוק מול בעלי הנכס האם יש אצלם תיעוד.

מבחינת הוועדה יש היתרים מאחר ויש טופס היתר חתום
עליכם לבדוק התאמה להיתרים עפי השטחים שכתובים בהיתרים ועפי תיאור הבקשה.

ספיר אלקובי מזכירת קבלת קהל, אגף תכנון והנדסה
טלפון: 08-9274087
sapirn@gezer-region.muni.il

מועצה אזורית גזר
המרחב הכפרי במרכז
gezer-region.muni.il

לאחר שיחה עם הלקוח מיום 18/02 נמסר שאין לו גם תיעוד לגרמושקות החסרות .

סטטוס קיים במשק

בהיתר
הגשת תוכניות הסדרה
להריסה/ הסדרה
פענוח השוואתי

1. בית מגורים ראשון
2. בית מגורים שני
3. סכבה חקלאית / לול
4. מוסך
5-6. קונטיינרים

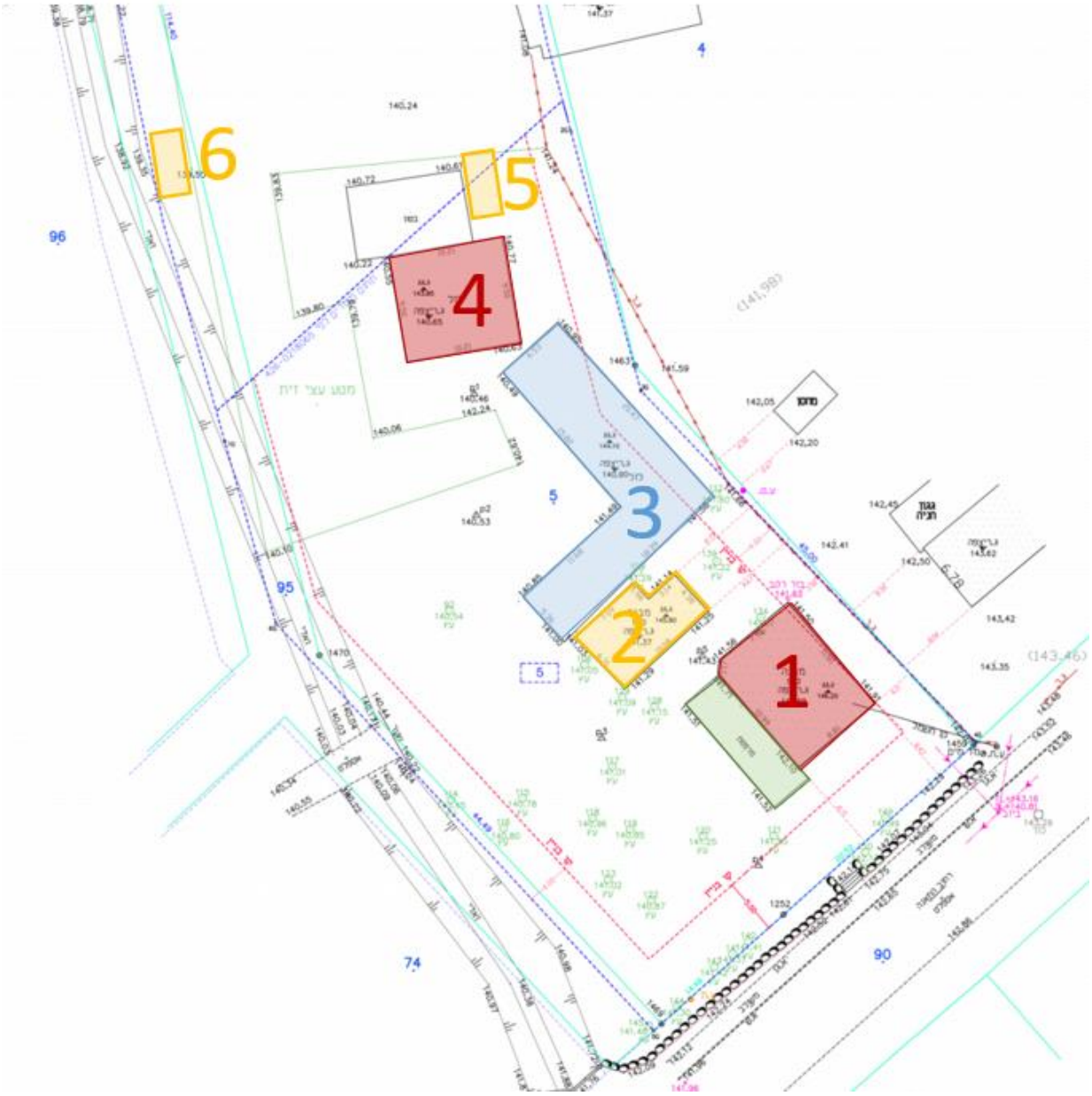

מתווה הסדרה

מבנה 1 - בית מגורים ראשון:

סטטוס: לאחר בדיקת מפת המדידה בשילוב הלוויין, נמצא ששטחי המגורים בבית מגיעים לגודל של כ- **104 מ"ר** + כ- **47 מ"ר** מרפסת מקורה. קיימים טפסי היתר למשק משנים 1968, 1978, 1983 המתירים הריסת בית ישן ובניית בית מגורים בגודל **60.76 מ"ר** + הקמת מרפסת לבית מגורים קיים + כיסוי מרפסת בגודל **46.4 מ"ר**. המבנה חורג מקו בניין צידי.

השלכות: עפ"י המפורט בטפסי ההיתר, נראה כי בית המגורים עומד שלא בהתאם להיתר, שכן בפועל הבית מגיע לשטח של כ-104 מ"ר + מרפסת מקורה בשטח של כ-47 מ"ר לעומת טפסי ההיתר בהם מופיע בית מגורים בגודל 60.67 מ"ר + מרפסת מקורה 46.4 מ"ר. קיים פער של כ-43 מ"ר בגודל בית המגורים. לא ייגבו כל דמי שימוש בגין המבנה.

יש להסדיר את המבנה בהתאם למצבו הנוכחי. בית המגורים קטן מ-160 מ"ר ועל כן לא יגבו בגינו כל דמי היתר. ככל ומזמין הבדיקה יבחר להרחיב את הבית לשטח מעבר ל-160 מ"ר יחולו דמי היתר המוערכים בכ-8,600 ₪ למ"ר עיקרי ובכ-4,300 ₪ למ"ר שירות נכון לתאריך הבדיקה לקחת בחשבון שיידרש פתרון מיגון במסגרת ההסדרה של הבית.

במידה ומזמין הבדיקה רוצה לפנות את הבית בנ"ל ולבנות במקומו בית מגורים חדש, יש לסמן את המבנה להריסה. הקמת הבית החדש עד לשטח של 160 מ"ר תהיה פטורה מתשלום דמי היתר. במידה והבית יעבור את ה-160 מ"ר יחול תשלום דמי היתר המוערך בכ- 8,600 ₪ למ"ר עיקרי ובכ- 4,300 ₪ למ"ר שירות נכון לתאריך הבדיקה.

המבנה חורג מקו בניין צידי. הוראות התב"ע קובעות כי מבנים שהיו קיימים בהיתר לפני אישור תכנית זו לא יחשבו כחורגים מהוראות התכנית לעניין קווי הבניין. מכיוון שלא נמצאו התכניות לבית המגורים ולא ניתן לדעת איזה חלק מהבית הינו בהתאם להיתר. קיימת חשיפה לכך שהוועדה המקומית תדרוש את הסדרת המבנה במסגרת קווי הבניין. במצב זה יש להרוס את החלק החורג מקו הבניין או לחלופין להגיש תב"ע נקודתית לתיקון קווי בניין בצורה שתכלול את המבנה בתוכה.

הוראות טבלה 5:

א.. אין בתכנית זו כדי לפגוע במבנים שנבנו כדין ערב אישור התכנית. מבנים קיימים שאושרו בהיתר כדין לא יחשבו כחורגים מהוראות התכנית לעניין קווי הבניין בתכנית זו. בניה חדשה בהתאם לתכנית זו תהיה בהתאם לקווי הבניין הקבועים בתכנית.

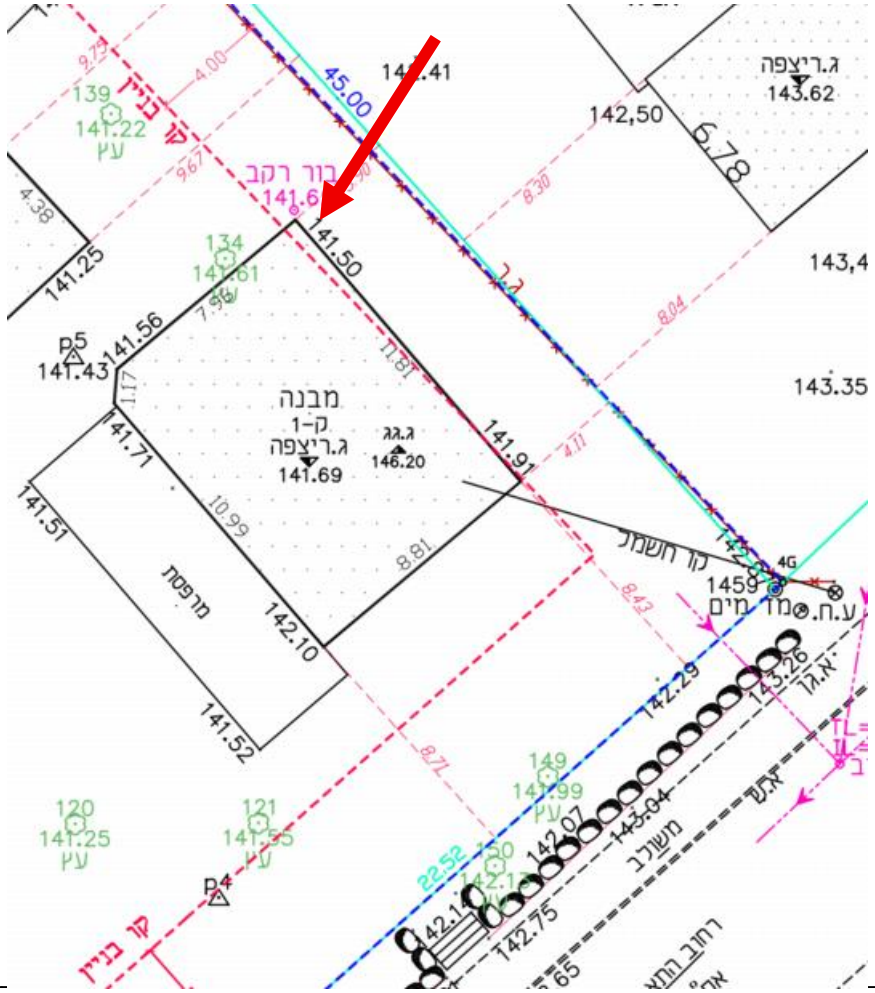

<u>מבנה 2 - בית מגורים שני:</u>

<u>סטטוס:</u> לאחר בדיקת מפת המדידה בשילוב הלווין, נמצא ששטחי המגורים בבית מגיעים לגודל של כ- **60 מ"ר**. לא נמצא כל היתר עבור המבנה.

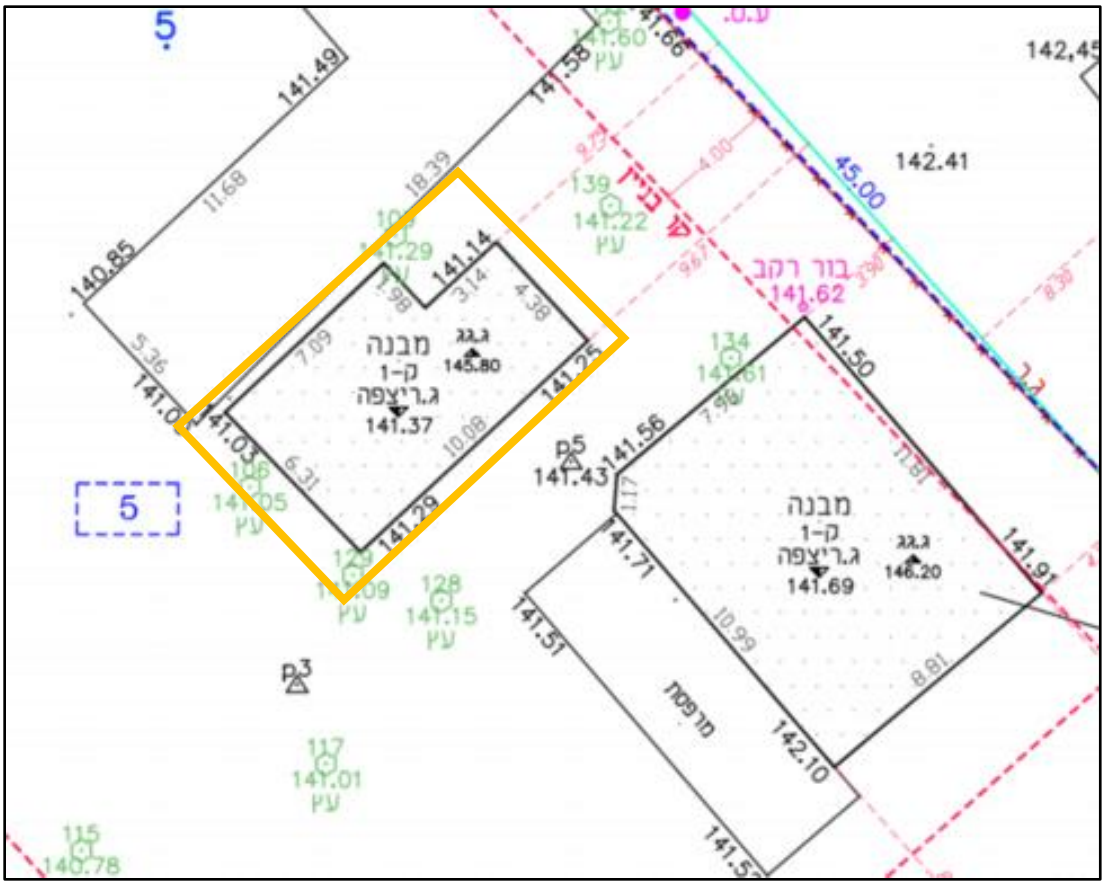

<u>השלכות:</u> בית המגורים עומד ללא היתר ומהווה בית מגורים שני בנחלה. על כן קיימת בגינו חשיפה לדמי שימוש המוערכים בכ- 25,000 ₪ עבור כל שנה עד שנתיים אחורה ובסה"כ כ- 50,000 ₪.

יש להסדיר את המבנה בהתאם למצבו הנוכחי. מכיוון שבית המגורים מגיע לשטח שאינו עולה על 160 מ"ר, בעת הסדרתו לא יחול תשלום דמי היתר. במידה והבית יורחב ויוגש בתוכניות מעבר ל-160 מ"ר יחולו דמי היתר המוערכים בכ-8,600 ₪ למ"ר עיקרי ובכ-4,300 ₪ למ"ר שירות נכון לתאריך הבדיקה. יש לקחת בחשבון שיידרש פתרון מיגון במסגרת ההסדרה של הבית.

כפי שנמסר לנו ע"י מזמין הבדיקה, בכוונתו לבחון אפשרות להריסת הבית הקיים ובניית בית מגורים חדש במקומו. בכדי להקים בית חדש במקום הבית הקיים, יש לסמן את הבית הנוכחי להריסה. במידה והבית החדש יהיה בשטח שאינו עולה על 160 מ"ר, בעת

הקמתו לא יחול תשלום דמי היתר. במידה ויגיע לגודל של מעבר ל-160 מ"ר, בעת הסדרתו יחול תשלום דמי היתר המוערך בב- 8,600 ₪ למ"ר עיקרי ובב- 4,300 ₪ למ"ר שירות נכון לתאריך הבדיקה.

מבנה 3 – לול / סככה חקלאית:

סטטוס: לאחר בדיקת מפת המדידה, נמצא ששטח המבנה מגיע לגודל של כ- **198 מ"ר**. קיימים טפסי היתר למשק משנים 1971, 1975 המתירים הקמת לול ותוספת סככת משק. המבנה חורג מקו בניין צידי.

השלכות: לא ניתן לדעת האם המבנה עומד בהתאם להיתר. טפסי ההיתר הקיימים ללול וסככת משק אינם מפרטים שטחים. בהתאם להנחיית הוועדה המוצגת מעלה נראה כי מכיוון שלא ניתן להתאים את המבנה לטופס ההיתר לא יכירו במבנה כקיים בהיתר. לא ייגבו כל דמי שימוש בגין המבנה. יש לבצע פרה רולינג מול הוועדה המקומית האם המבנה יידרש בהסדרה או לא.

אם מזמיני הבדיקה סבורים כי המבנה עומד מלפני שנת 1965, יש לערוך למבנה פענוח השוואתי. במידה והמבנה יימצא תואם בגודלו, מיקומו ושימושו המבנה יהיה פטור מהיתר. במידה ולא יעמוד בתנאי הפענוח המבנה יידרש בהסדרה.

המבנה חורג מקו בניין צידי. בכדי להסדיר את המבנה יש להרוס את החלק החורג מקו הבניין. לאחר מכן יש להגיש את המבנה להיתר בניה במסלול חקלאי ועל כן להוכיח זיקה לחקלאות בהיקף נרחב מספיק בהתאם לטבלאות משרד החקלאות המפורטות בסוף הבדיקה.

מבנה 4 – מוסך (פל"ח):

סטטוס: לאחר בדיקת מפת המדידה בשילוב הלוויין, נמצא ששטח המבנה מגיע לגודל של כ- **98 מ"ר** מוסך + משרד כ-**10 מ"ר**. לא נמצא כל היתר עבור המבנה.

השלכות: המבנה עומד ללא היתר ומהווה מבנה פל"ח בנחלה. על כן קיימת בגינו חשיפה לדמי שימוש המוערכים בכ- 16,000 ₪ לכל שנה עד 7 שנים אחורה ובסה"כ כ- 113,000 ₪. יש להסדיר את המבנה או לפנות אותו.

בכדי להסדיר את המבנה יש להגישו להיתר בניה במסלול פל"ח.
השימוש הקרוב ביותר לשימוש שנעשה בפועל הוא מלאכה ותעשיה זעירה.
יש לשים לב כי וועדות התכנון והבניה פעמים רבות לא מכירות במוסך כתואם את השימושים המותרים על פי התב"ע. ולכן נדרש לאישור עקרוני שלהם טרם הבקשה להיתר. במידה והוועדה המקומית לא תכיר בשימוש של המוסך כשימוש שמוגדר תחת מלאכה ותעשייה זעירה תהיה רשאית הוועדה המקומית לדרוש התאמה של השימוש הקיים לשימוש הרצוי בהיתר ע"י התאמות בפועל בשטח.
הסדרת המבנה לשימוש מלאכה ותעשייה זעירה כאמור תהיה כרוכה בתשלום דמי היתר המוערך בכ- 3,000 ₪ לכל מ"ר ובסה"כ כ- 294,000 ₪. על תשלום זה יש להוסיף מס רכישה 6% כחוק. יש לקחת בחשבון כי בעת הסדרת המבנה יידרש פתרון מיגון בהתאם להנחיות פיקוד העורף. בעת הסדרת המבנה יש לשים לב כי במסגרת התב"ע לפל"ח קיימות מגבלות לעניין מרחק מבני פל"ח ממבנים שונים נחלה גובלת.

מרווחים		
מרחק בין מבנה פל"ח לכל מבנה אחר בנחלה	מרחק בין מבנה פל"ח לכל מבנה מגורים בנחלה גובלת	מרחק בין מבנה פל"ח לבין כל מבנה שאיננו למגורים בנחלה גובלת
עד 0 מ'	מינ' 25 מ'	מינ' 8 מ'

מבנים 5-6 קונטיינרים:

סטטוס: לאחר בדיקת מפת המדידה בשילוב הלווין, נמצא כי המבנים עומדים ובגדלים הבאים:

- מבנה 5: קונטיינר בגודל 12 מ"ר, ללא היתר.
- מבנה 6: קונטיינר בגודל 12 מ"ר, ללא היתר. המבנה חורג מקו בניין צידי.

השלכות: המבנים עומדים ללא היתר ומהווים מחסנים המשמשים את המוסך. על כן קיימת בגינם חשיפה לדמי שימוש המוערכים בכ- 3,600 ₪ לכל שנה עד 7 שנים אחורה ובסה"כ כ- 25,000 ₪. יש להסדיר את המבנים או לפנות אותם.

המבנים עומדים מחוץ לחלקת המגורים, מבנה 6 חורג מקו בניין צידי. ניתן להסדיר את המבנים כמבנים חקלאיים. בכדי להסדיר את המבנים כאמור יש לקבל הסכמה לבניה בקו בניין 0 למבנה 6 או למקמו במסגרת קווי הבניין. לאחר מכן יש להגיש את המבנים להיתר בניה במסלול חקלאי ועל כן להוכיח זיקה לחקלאות בהיקף נרחב מספיק בהתאם לטבלאות משרד החקלאות המפורטות בסוף הבדיקה.

קיימת אפשרות להסדיר את המבנים כמבני אחסנה המשמשים את המוסך. בכדי להסדירם כאמור יש למקם את המבנים בתוך חלקת המגורים. לאחר מכן יש להגישם להיתר בניה במסגרת פל"ח. הסדרה כאמור תהיה כרוכה בתשלום דמי היתר המוערך בכ-3,000 ₪ לכל מ"ר. על תשלום זה יש להוסיף מס רכישה 6% כחוק.

BoosT
החברה לפיתוח נכסים

מתווה להקמת בית שלישי

הקמת בית המגורים השלישי תתאפשר רק לאחר הסדרה של המשק וכניסה לאחד ממסלולי החכירה (היוון) שתוארו קודם ולאחר כניסת תב"ע המוסיפה זכות לבית שלישי לתוקף. לאחר הסדרת המצב בנוי (לא כולל פרגולות) וכניסה למסלול בדמי חכירה יחויבו דמי היתר על כל מ"ר מעבר ל-375 מ"ר מכלל מבני המגורים בנחלה (בית ראשון 104, בית שני עד 60).

על הבתים להיבנות בגבולות ה-2.6 דונם (שטח צהוב) כאשר נבחר מתוכם 2.5 דונם (מקוקו אדום) שבהם יתכנסו כלל המבנים בחלקת המגורים. – המוצג להמחשה בלבד ואינו בהתאם לגדלים מדויקים.

לאחר הסדרת המצב הקיים והיוון המשק יישארו **211** מ"ר פטורים מדמי היתר להקמת בית שלישי, מ"ר אלו יחויבו בהיטל השבחה המוערך בכ- 4,700 ₪ למ"ר. מעבר לכך יחויב כל מ"ר בדמי היתר המוערכים בכ-8,600 ₪ למ"ר עיקרי ובכ- 4,300 ₪ למ"ר שירות נכון לתאריך הבדיקה.

מתווה להקמת פל"ח

כחלק מבדיקת ההתכנות הועלתה האפשרות להקמת מבני פל"ח בנחלה. יש להדגיש כי הקמת מבני פל"ח צריכה להיות במסגרת ה2.5 דונם בתוך חלקת המגורים. בכדי להקים מבנה פל"ח או להסדיר מבנה קיים יש להגיש היתר בניה שיכלול תשלום דמי היתר לרמ"י בהתאם לשימוש שייבחר למבנה.

בהתאם לשימושים במותרים בתב"ע, יהיה ניתן להקים מבנים לפעילות צימרים תחת הגדרת מבנה קייט כפרי במסגרת פל"ח ובהיקף של עד 4 יחידות בשטח של 25-40 מ"ר לכל יחידה. דמי היתר לצימרים מוערכים בכ- 2,900 ₪ לכל מ"ר. על הסכומים הנ"ל יש לקחת מס רכישה כחוק.

בעת הקמת צימרים יש לשים לב כי קיימת מגבלת מרחק ממבנה מגורים של 10 מ'.

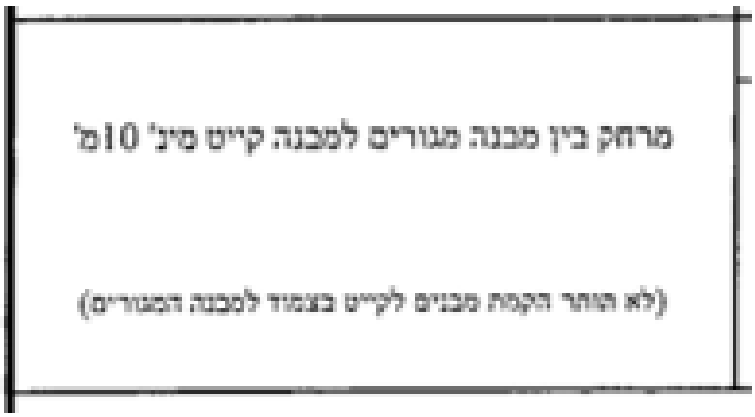

נספח גדלי מבנים בהתאם להיקף חקלאות

שטחי מבנים חקלאיים (מ"ר) - גידולים צימחיים

הענף	סוג הגידול	מיקום כללי	מיקום במשק משפחתי	גודל שטח מעובד	שטח אריזה ומיון	שטח קירור	שטח מחסן שירות	שירותים, מקלחות, חדר אוכל ומטבח	סככת ציוד וכלים חקלאיים	ס"ה שטח	הערות
מטעים	נשירים וסובטרופים	שטח מבונה	חלקה א	20 עד 150 דונם	320	100	100	60	150	730	
	נשירים וסובטרופים	שטח מבונה	חלקה א	150 עד 300 דונם	380	100	100	60	250	890	
	בשטח פתוח	שטח פתוח	גם חלקה ב וג	מעל 40 ד'	0	0	0	0	250	250	מפולשת. מחסן 20 מ"ר כחלק מהסככה.
	כרם מאכל	שטח מבונה	חלקה א	20 עד 150 דונם	300	100	100	60	150	710	
	כרם מאכל	שטח מבונה	חלקה א	150 עד 300 דונם	470	100	100	60	250	980	
	כרם מאכל	שטח פתוח	גם חלקה ב וג	מעל 60 ד'	0	0	0	0	250	250	מפולשת. מחסן 20 מ"ר כחלק מהסככה.
	כרם יין	שטח מבונה	חלקה א	20 עד 100 דונם	0	0	100	60	40	200	
	כרם יין	שטח מבונה	חלקה א	מעל 100 ד'	0	0	100	60	160	320	
	כרם יין	שטח פתוח	גם חלקה ב וג	מעל 60 ד'	0	0	0	0	250	250	מפולשת. מחסן 20 מ"ר כחלק מהסככה.
	בננות	שטח מבונה	חלקה א	20 עד 150 דונם	360	100	100	60	150	770	
	בננות	שטח מבונה	חלקה א	150 עד 300 דונם	360	100	100	60	250	870	
	בננות	שטח פתוח	גם חלקה ב וג	מעל 150 ד'	0	0	0	0	250	250	מפולשת. מחסן 20 מ"ר כחלק מהסככה.
	שקדים	שטח מבונה	חלקה א	מינימום 50 ד'	0	0	100	0	150	250	
	שקדים	שטח פתוח	גם חלקה ב וג	מעל 50 ד'	0	0	0	0	150	150	מפולשת. מחסן 20 מ"ר כחלק מהסככה.
	זיתים	שטח מבונה	חלקה א	מינימום 50 ד'	0	0	100	0	150	250	
	זיתים	שטח פתוח	גם חלקה ב וג	מעל 50 ד'	0	0	0	0	150	150	מפולשת. מחסן 20 מ"ר כחלק מהסככה.
	הדרים	שטח מבונה	חלקה א	מינימום 50 ד'	300	110	100	60	150	720	
	הדרים	שטח מבונה	חלקה א	50 עד 180 דונם	450	200	100	60	150	960	
	הדרים	שטח פתוח	גם חלקה ב וג	אין בניה	0	0	0	0	0	0	
	תמרים, תאנים, שסק וכו'	שטח מבונה	חלקה א	20 עד 150 דונם	320	100	100	60	150	730	
	תמרים, תאנים, שסק וכו'	שטח פתוח	גם חלקה ב וג	אין בניה	0	0	0	0	0	0	
ירקות	פלפל	שטח מבונה	חלקה א	20 עד 50 ד'	400	60	100	60	150	770	
	פלפל	שטח מבונה	חלקה א	50 עד 150 דונם	600	80	100	60	250	1,090	
	מלונים	שטח מבונה	חלקה א	20 עד 50 ד'	400	60	100	60	150	770	
	מלונים	שטח מבונה	חלקה א	50 עד 150 דונם	600	80	100	60	250	1,090	
	עגבניות שרי	שטח מבונה	חלקה א	20 עד 50 ד'	300	60	100	60	150	670	
	עגבניות שרי	שטח מבונה	חלקה א	50 עד 150 דונם	500	80	100	60	250	990	
	תבלינים טריים	שטח מבונה	חלקה א	10 עד 30 דונם	300	80	100	60	150	690	
	תבלינים טריים	שטח מבונה	חלקה א	30 עד 150 דונם	500	120	100	60	150	930	

שטחי מבנים חקלאיים (מ"ר) - גידולים צימחיים

הענף	סוג הגידול	מיקום כללי	מיקום במשק משפחתי	גודל שטח מעובד	שטח אריזה ומיון	שטח קירור	שטח מחסן שירות	שירותים, מקלחות, חדר אוכל ומטבח	סככת ציוד וכלים חקלאיים	ס"ה שטח	הערות
ירקות	ירקות אחרים	שטח מבונה	חלקה א	20 עד 50 ד'	300	60	100	60	150	670	
	ירקות אחרים	שטח מבונה	חלקה א	50 עד 150 דונם	500	80	100	60	250	990	
	פטריות	שטח מבונה	חלקה א		400	0	0	0	0	400	
	תות שדה	שטח מבונה	חלקה א	10 עד 50 דונם	100	20	60	60	150	390	
	כללי	שטח פתוח	גם חלקה ב וג	מינימום 50 ד'	0	0	20	0	100	120	
	תות שדה	שטח פתוח	גם חלקה ב וג	מינימום 20 ד'	0	0	0	0	150	150	מפולשת. מחסן 20 מ"ר כחלק מהסככה.
פרחים	פרחים	שטח מבונה	חלקה א	10 עד 30 דונם	240	60	100	60	150	610	
		שטח מבונה	חלקה א	30 עד 100 דונם	500	60	100	60	150	870	
		שטח פתוח	גם חלקה ב וג	אין בניה	0	0	0	0	0	0	
דבש	מכון רדיה	שטח מבונה	חלקה א	3,500 כוורות	340		100	60	500	1,000	תתאפשר גמישות בין סככות ציוד וכלים חקלאיים לשטחי אריזה ומיון (ניתן להמיר לשטח קירור עד 250 מ"ר מהיקף השטח הכולל).
שחת, קש	מתבן לאחסנת תוצרת	שטח מבונה	חלקה א							1,000	גודל המבנה ייקבע בהתייעצות עם מדריך שה"מ
ח. צמחית	מחסן חקלאי בסיסי	שטח מבונה	חלקה א	מינימום 7 דונם ועד 19 דונם	0	0	40	0	60	100	ניתן להגדיל את גודל הסככה המפולשת (סככת ציוד וכלים חקלאיים) עד להיקף של 110 מ"ר (סה"כ 150 מ"ר).
קנאביס רפואי	קנאביס רפואי - מבנה לטיפול ראשוני, אריזה ומיון.	שטח מבונה	חלקה א'/שטח למבני משק		1720	60	100	60	60	2,000	תתאפשר גמישות בחלוקת גדלים אחרת בין השימושים השונים.
		שטח פתוח	חלקה ב/ג		530	60	40	60	60	750	תתאפשר גמישות בחלוקת גדלים אחרת בין השימושים השונים.

הערות

1. יש לראות בנתוני הטבלה המלצות מקצועיות על פיהן ניתן לקבוע את המלצת המשרד ביחס לגודל מבנה.
2. גודל שטח מעובד הינו טווח המאפשר להמליץ על היקף בינוי נדרש ולא בהכרח את המקסימום האפשרי.
3. מדובר בסדרי גודל. תתאפשר גמישות במידה וקיימים נתונים מקצועיים המצדיקים שינוי הנתון.
4. על מנת לתמוך בשינויים אלה נדרשת חוות דעת מדריך מקצוע ובלבד ששינוי המסגרת לא יחרוג מתוספת של 30%.
5. גודל מתבן לאחסנת תוצרת לא יעלה על 1,000 מ"ר ויקבע בהתאם להיקף הגידול ולצורך אחסנת תוצרת מקומית בלבד.
6. גידול קנאביס במבנה מבוקר (Indoor) יתאפשר רק מתוקף תכנית מפורטת (תב"ע), או בשטח בייעוד מבני משק, או כחלק ממבנה קיים ומאושר לטיפול בתוצרת חקלאית בייעוד חקלאי בחלקה א' או בייעוד מבני משק לאחר הוכחת גידול בחממות.

שטחי מבנים חקלאיים (מ"ר) בעלי חיים

הענף	סוג המבנה הנדרש	יחידת מידה	שטח ליחידה	הערות כלליות
רפת בקר לחלב	כל המבנים - מפתח כללי כולל כל המבנים לרבות מתבן, מאצרה וכו'	חולבת	60	היקף הגידול נמדד לפי מספר החולבות והעדר כולל חולבות ועגלים מתוצרת הרפת. גידול עגלים מחושב בנפרד. ניתן להמליץ על תוספת של 30% עבור סככות לשירות גידול עתידי במידת הצורך.
שטח מבנים וסככות כולל	סככות, מעברים, מבני שירות, יונקיה	מ"ר לכל חולבת	36	
עד 100 פרות	מכון חליבה, חצר המתנה ומבני שירות	מ"ר	410	
מ- 101 עד 300 פרות	מכון חליבה, חצר המתנה ומבני שירות	מ"ר	480	
מ- 301 עד 750 פרות	מכון חליבה, חצר המתנה ומבני שירות	מ"ר	725	
מ- 751 ויותר פרות	מכון חליבה, חצר המתנה ומבני שירות	מ"ר	975	
יונקיה	סככה	מ"ר לכל חולבת	10	
מאצרת זבל	מבנה מקורה	מ"ר לכל חולבת	5	בהתאם לדרישות איכה"ס.
מתבן	מתבן	מ"ר לכל חולבת	3	
עד 100 פרות	מתבן אחד	מ"ר	350	
מ- 101 עד 300 פרות	2 מתבנים - שטח כולל	מ"ר	800	
מ- 301 עד 750 פרות	5 מתבנים - שטח כולל	מ"ר	2,000	
מ- 751 עד 900 פרות	6 מתבנים - שטח כולל	מ"ר	2,400	
בקר לבשר		עגל		
מפטמה בתחום בנוי	שטח שיכון לעגלים	מ"ר לכל עגל	10	גודל עדר מינימלי 100 ראש.
מפטמה בתחום בנוי	מתבן ל-1000 עגלים	מ"ר	500	
בקר במרעה				
בשטח פתוח / בשטחי מרעה	סככה מפולשת	מקסימום - מ"ר	80	גודל עדר מינימלי 100 ראש. ללא סככות גידול.
	מחסן שירות	מקסימום - מ"ר	20	
	מתבן	מקסימום - מ"ר	150	
	מרכז מזון	מקסימום - מ"ר	200	
צאן לחלב בשטח בנוי				אין לאשר בשטח פתוח
צאן לחלב בשטח בנוי	שטח שיכון - סככה וחצר	מ"ר לעז או כבשה חולבת	5	
	שטח שיכון - סככה וחצר	מ"ר לצפירה או שיה	5	
	מתבן	מ"ר לראש	1.5	מתבן למגדל חדש בדיר חדש עד 200 מ"ר.
	מרכז מזון מקורה	מ"ר לראש	1.5	מרכז מזון למגדל חדש בדיר חדש עד 200 מ"ר.
עד 300 כבשים	מכון חליבה, חצר המתנה, מחסן, מ.שירות	מ"ר	365	
	מבנה מכון	מ"ר	110	לפי 48 עמדות
	חצר המתנה	מ"ר	150	לפי 100 ראש בקבוצה ו2 קבוצות במקביל

הענף	סוג המבנה הנדרש	יחידת מידה	שטח ליחידה	הערות כלליות
עד 300 כבשים	מחסן, שירותים, חדר חלב	מ"ר	105	
מ- 301 עד 1000 כבשים	מכון חליבה, חצר המתנה, מחסן, מ.שירות	מ"ר	485	
	מבנה מכון	מ"ר	130	לפי 60 עמדות
	חצר המתנה	מ"ר	225	לפי 150 ראש בקבוצה ושתי קבוצות במקביל
	מחסן, שירותים, חדר חלב	מ"ר	130	
צאן לחלב בשטחי מרעה	שטח שיכון - סככה וחצר	מ"ר לעז או כבשה בוגרת, לצפירה או שיה	3	מגדל חדש – 100 ראש לפחות סככות שיכון בגודל 450 מ"ר מעל 200 ראש – 900 מ"ר לכל היותר. במקרים מיוחדים, בהיקפי גידול גדולים משמעותית ובהתאמה להיקפי שטח המרעה, ניתן לשקול הגדלת סככות השיכון עד ל1,200 מ"ר.
	מתבן	מ"ר	200	
	מחסן	מ"ר	30	
	סככת כלים	מ"ר	80	
	מכון חליבה	מ"ר	150	
צאן לבשר				
צאן לבשר בשטח בנוי	שטח שיכון - סככה וחצר	מ"ר לעז או כבשה בוגרת, לצפירה או שיה	5	מגדל חדש - 100 ראש לפחות ועד 200 ראש לכל היותר. עד 300 ראש - גודל הסככות יחושב לפי מספר הראשים הקיים כפול 2. בין 300 ל-400 ראש - עד 3,000 מ"ר. מעל 400 ראש - לפי מספר הראשים בפועל, בתוספת 1,000 מ"ר.
	מתבן	מ"ר לראש	1	מתבן למגדל חדש בדיר חדש עד 200 מ"ר, לעדר קיים לפי מפתח של 1 מ"ר לראש.
	מרכז מזון מקורה	מ"ר לראש	1	מרכז מזון למגדל חדש בדיר חדש עד 200 מ"ר, לעדר קיים, לפי מפתח של עד 1 מ"ר לראש.
	מחסן ומשרד כולל שירותים	מקסימום - מ"ר	100	לפי 20 מ"ר מחסן + 30 מ"ר מבנה שירות לעדר עד 400 ראש. מעל זה תוספת של 5 מ"ר לכל 100 ראש.
	סככת כלים	מקסימום - מ"ר	150	סככת כלים-עד 80 מ"ר לעדר של עד 400 אמהות. מעבר לכך 10 מ"ר נוספים לכל 100 ראש.
צאן לבשר בשטח פתוח	שטח שיכון - סככה וחצר	מ"ר לעז או כבשה בוגרת, לצפירה או שיה	4	מגדל חדש - 100 ראש לפחות ועד 200 ראש לכל היותר. עד 300 ראש - גודל הסככות יחושב לפי מספר הראשים הקיים כפול 2.
	מתבן	מ"ר לראש	1	מתבן למגדל חדש בדיר חדש עד 200 מ"ר, לעדר קיים לפי מפתח של 1 מ"ר לראש.
	מחסן ומשרד כולל שירותים	מקסימום - מ"ר	30	
	סככת כלים	מקסימום - מ"ר	80	
צאן לבשר בשטחי מרעה	שטח שיכון - סככה וחצר	מ"ר לעז או כבשה בוגרת, לצפירה או שיה	3	מגדל חדש – 100 ראש לפחות סככות שיכון בגודל 450 מ"ר מעל 200 ראש – 900 מ"ר לכל היותר. במקרים מיוחדים, בהיקפי גידול גדולים משמעותית ובהתאמה להיקפי שטח המרעה, ניתן לשקול הגדלת סככות השיכון עד ל1,200 מ"ר.
	מתבן	מ"ר	200	
	מחסן	מ"ר	30	
	סככת כלים	מ"ר	80	
לול מטילות				יש להעדיף מיקום מחוץ לנחלות בשטח חקלאי מיוחד או מבני משק וכד'
6,000 מטילות	מבנה לול	מ"ר	700	

הענף	סוג המבנה הנדרש	יחידת מידה	שטח ליחידה	הערות כלליות
12,000 מטילות	מבנה לול	מ"ר	1,000	
20,000 מטילות	מבנה לול	מ"ר	1,200	
40,000 מטילות	מבנה לול	מ"ר	1,500	
6,000 מטילות חופש או אורגני	מבנה לול	מ"ר	1,000	
6,000 מטילות מעוף (ללא כלובים)	מבנה לול	מ"ר	700	
6,000 מעוף (3 קומות כלובים)	מבנה לול	מ"ר	500	
מבנה שרות לחווה		מקסימום - מ"ר	60	
מחסן		מקסימום - מ"ר	100	בלול מעל 12,000 מטילות יותר מחסן גדול יותר עד 150 מ"ר.
לול פטם (לרבות רביה ובתי אימון)		252 טון בלול "בסיסי" בגודל 1200 מ"ר	1,200	לייצור 1000 טון בשנה יש צורך ב-4 לולים בסיסיים, כ-5000 מ"ר נטו בסה"כ
במתחם לולי פטם	מבנה שרות לחווה	מקסימום - מ"ר	60	
	מחסן	מקסימום - מ"ר	100	בלול מעל 2000 טון יותר מחסן גדול יותר עד 250 מ"ר.
לול פרגיות כבדות, רביה כבדה, רביה קלה, הודים, הודים - בתי אימון, הודים - לול פיטום	מבנה	מקסימום - מ"ר	1,000	
	מבנה שרות לחווה	מקסימום - מ"ר	60	
	מחסן	מקסימום - מ"ר	100	בלול מעל 2000 טון יותר מחסן גדול יותר עד 250 מ"ר.
אורווה				
	שטח שיכון וטיפולים לסוס כולל מחסן כלים וציוד	מ"ר לסוס	35	למגדל מתחיל המחזיק עד 2-5 סוסים בלבד, שטח האורווה על כל מרכיביה לא יעלה על 200 מ"ר.
	מחסן, שירות, שרותים, מקלחות	מקסימום - מ"ר	100	
	שרות- תצוגה, וטרינר, תרופות	מקסימום - מ"ר	60	
	מתבן בגובה 4 חבילות	מקסימום - מ"ר	350	
	מתבן בגובה 3 חבילות	מקסימום - מ"ר	490	
כלבייה				
בהתאם לכרטיס המבנה				
מדגה				
שטח פתוח	מחסן כלים	מ"ר	20	
	סככת כלים וציוד	מ"ר	80	מפולשת. מחסן 20 מ"ר כחלק מהסככה.
שטחי גידול (בריכות)	לפי המלצת מדריך			
מדגה אינטנסיבי	בריכות מקורות ו/או מבנה מבוקר לגידול			בהתאם להיקף הגידול ובכפוף להמלצת אגף הדיג.