12/02/2026

בדיקת התכנות משפחת מאיר מושב מסילת ציון

מטרות בדיקת ההתכנות:

- יצירת מתווה הסדרה למשק
- הערכת עלויות חריגות והסדרה
- תחשיבים להיוון 3.75%
- מתווה להקמת בית מגורים שלישי
- מתווה להקמת פל"ח

בדיקת ההתכנות התחלקה למספר שלבים:

1. סקירת החומרים וקבלת סטטוס עדכני- סריקת מפת מדידה שהתקבלה, סריקה של כלל ההיתרים, סקירת התב"ע הקיימת ותבע"ות אחרות רלוונטיות, השוואת ההיתרים למצב הקיים ואיתור חריגות.

2. הקמת מתווה הסדרה למשק – תחשיבי הערכת עלויות הגשה במצב קיים, ופתרונות הסדרה לקיים במשק.

3. ביצוע תחשיבי פיתוח – עלויות רכישת זכויות מהוונות 3.75% או 33%, עלויות דמי היתר למגורים, תחשיבי פל"ח ותחשיבי פיצול.

4. יצירת מתווה תכנוני – על פי המצב הקיים בנחלה, בהתאמה למפת המדידה הנוכחית והתוכנית העתידית למשק.

שווי הזכויות בנחלה הסתמך על נתונים וסריקת שמות בסביבה משנים 2024-2025. בדיקת ההתכנות בוצעה על סמך גבולות התב"ע הנוכחית. **דמי ההיתר והנחיות רמ"י שבבדיקה הינם בהתאם למועד הבדיקה ויכולים להשתנות והינם מתעדכנים בהתאם למועד הגשת הבקשה לרמ"י.**

מזמין העבודה מודע לכך שלא בוצעה שומה למשק, ושהערכות אלו בוצעו לשם קבלת סדר גודל ראשוני בלבד ואינם מהוות אסמכתא משפטית.
בדיקת ההתכנות לא כוללת בתוכה חישובי אגרות בניה מיסים והיטלים.

העבודה בוצעה על פי מפות מדידה מצביות מיום 11/02/2026 ע"פ תב"עות מי/511 ו- מי/511/ב אשר מציינות את שטחי המבנים וגבולותיהם החיצוניים בלבד ועל כן קיימת מגבלה לבחינת המצב הבנוי הפנימי של המבנים, גבהים וחזיתות.

בדיקת התכנות זו הוכנה עבור מזמינה ולמטרתה בלבד. אין היא מהווה תחליף לייעוץ משפטי ו/או לשומה שנערכה על ידי שמאי מקרקעין מוסמך ואין להסתמך עליה לכל מטרה אחרת. השימוש בה נאסר על כל צד שלישי שהוא אינו המזמין, ועורכי בדיקת ההתכנות לא יהיו אחראים להסתמכות כלשהי כאמור. מובהר, כי בדיקה זו אינה מהווה תחליף לייעוץ מקצועי.

ניתוח תב"ע קיימת

על המושב חלה בין היתר תב"ע מי/511, עיקרי הזכויות נובעות גם מכוח תוכניות מי/200/ב ו- 151-0387068 והם (בהתחשב במגרש ההשלמה):

- הקמת בית מגורים 200 מ"ר עיקרי ושירות + 30 מ"ר מרתף למבנה
- יחידה צמודת קיר 50 מ"ר
- הקמת בית מגורים שלישי 140 מ"ר עיקרי + 20 מ"ר שירות
- בריכת שחייה

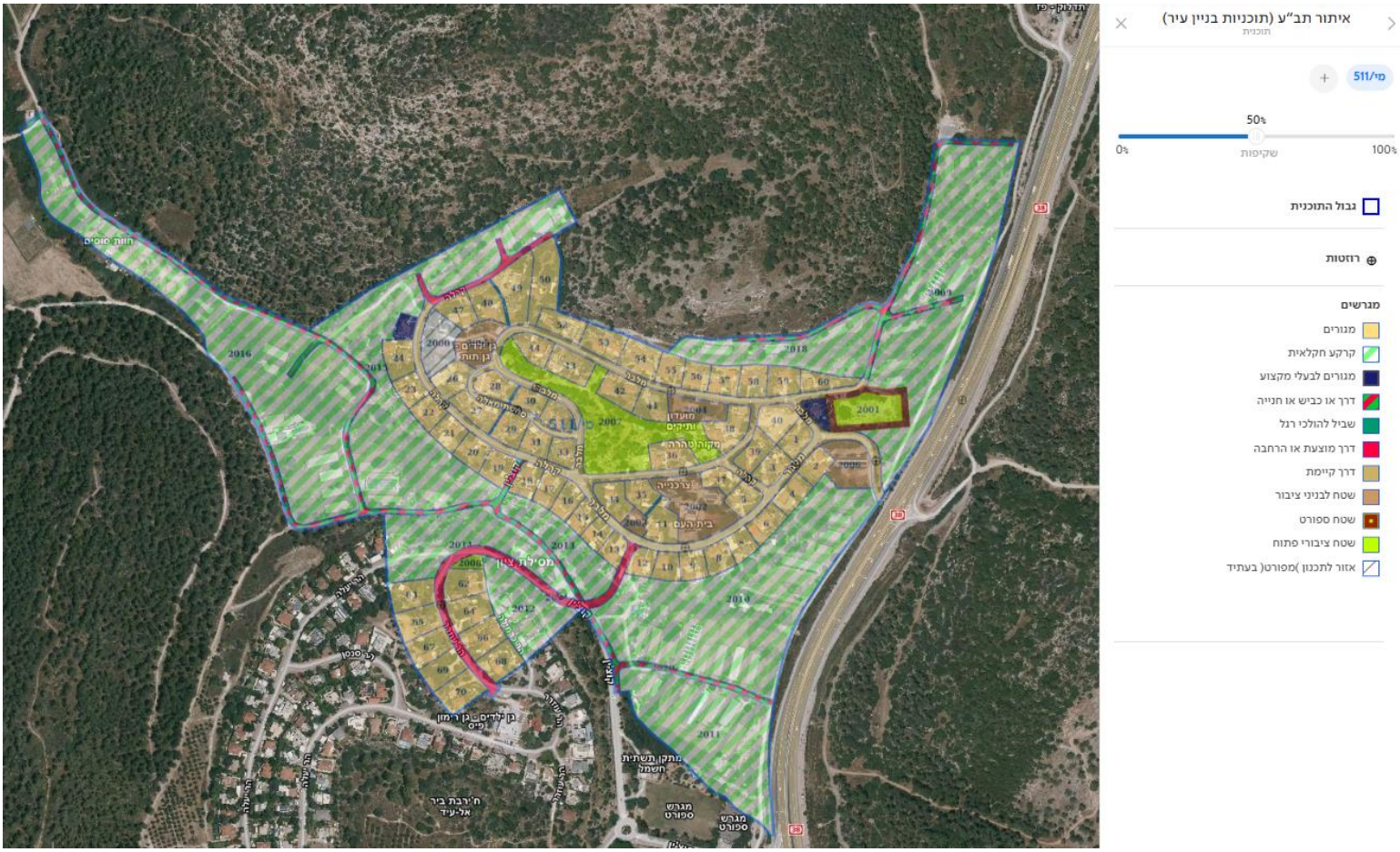

בנוסף על הנחלה קיימת תב"ע מי/511/ב המגדירה מגרשי מגורים שיהוו מגרשי השלמה לנחלות קיימות בהן אין אפשרות להקמת מבנה מגורים נוסף. עיקרי זכויות הבניה במגרש ההשלמה הנובעות מתכנית זו והם:

- הקמת בית מגורים בשטח 200 מ"ר עיקרי ושירות + חניה מקורה 30 מ"ר

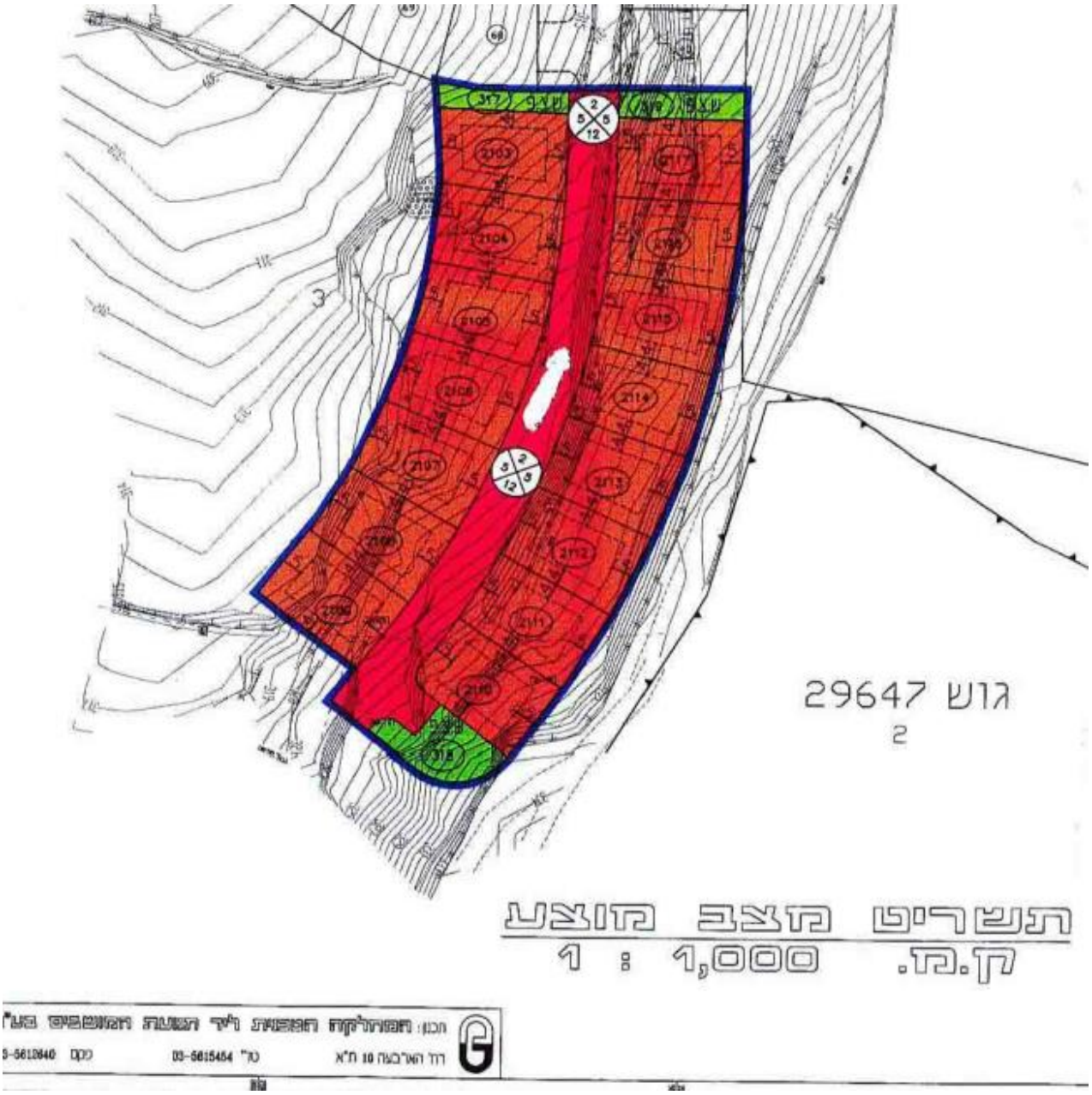

תב"ע לפל"ח

תוכנית 151-0387068 מאפשרת הקמת מבנים לפעילות שאינה חקלאית עד 350 מ"ר.

קבוצות שימושים	השימושים לתיירות כפרית ולמבנים חקלאיים מחולקים לפי קבוצות: קבוצה 1 - שימושים חקלאיים: גידולים חקלאיים לסוגיהם, לרבות חממות ובתי צמיחה לסוגיהם (כולל מחסנים, מבני שירות וסככות) וגידול בע"ח. קבוצה 2 שימושים בזיקה לפעילות חקלאית: (א)עיבוד תוצרת חקלאית - מבנים, מתקנים ומפעלים המשמשים לטיפול ועיבוד תוצרת חקלאית, כפעילות משלימה לפעילות החקלאית. לדוגמא: יקב, בית בד, רדיית דבש במכוורת, מחלבה, מבשלה, מגבנה, וכד'. (ב)חקלאות תיירותית - תיירות זו כוללת פתיחת המשק החקלאי לביקורי קהל. מדובר בפעילות חקלאית לכל דבר, אשר נלווה לה היצע תיירותי כגון: גידול פירות אקזוטיים, משתלה לריבוי ייחורים וגידול צמחים, גידול קקטוסים וצמחים מיוחדים, גידול תבלינים וצמחי מרפא, שיתוף המבקרים בקטיף פרי או פרחים וכד' (ג)גידול בע"ח מיוחדים- כמוקד למשיכת מבקרים: גידול ציפורים, דגי נוי, זוחלים, סוסים וכד', פינות חי וכו'. קבוצה 3 תיירות כפרית: (א)חדרי אירוח (ב)שירותי בילוי ונופש לגיוון שהות האורחים במקום: ספא, חדר התכנסות, חדר כושר וכו'. (ג)הסעדה (ד)מכירה של תוצרת בזיקה לפעילות החקלאית ו/או התיירות הכפרית ביישוב קבוצה 4 שימושים "תומכי תיירות" - כגון: גלריות וסדנאות אומן, חנויות מלאכת יד ומזכרות, עסקים המבוססים על מלאכות בית ושימושים דומים.

שירותי פנאי ונופש	מבנה המיועד לגוון שהות האורחים במקום דוגמת ספא, חדר התכנסות, חדר כושר.

3.1. השטח בו ניתן להתיר פיתוח שימושי תיירות כפרית מקבוצות 3 ו-4 בנחלה הינו תחום המגורים / אזור חקלאי עם הנחיות מיוחדות / אזור חקלאי ב' בשטח של 2.5 דונם בראש החלקה.

3.2. ניתן להתיר שימושים תומכי פעילות חקלאית (קבוצה 2) במבנה, הקיים כדין, גם אם חלק מהמבנה חורג מתחום השטח בו ניתן להתיר פיתוח כאמור לעיל (או צמוד דופן לו), מקווי בניין ומהגובה המרבי.

3.3. בכפוף לאמור בסעיפים 4.1.2 ב' ו 6.12, סה"כ שטחי הבניה המותרים לכל שימושי התיירות הכפרית בנחלה, לא כולל שימושים חקלאיים, לא יעלה על 350 מ"ר מרבי (עיקרי +שרות).

3.6. קווי בניין

ככל הניתן, קווי הבניין למגורים ולתיירות כפרית יהיו בהתאם לקבוע בתכנית המאושרת החלה במקום, למעט מבנים קיימים בשטח בעת תחילתה של תכנית זו. עבור מבנים למגורים ותיירות כפרית הנוספים מכוח תכנית זו, רשאי מוסד התכנון המוסמך לקבוע קווי בנין של עד 3 מ'. ישמר קו בניין מינימאלי של 3 מטרים עבור מבנה מגורים הגובל בשטח פתוח.

היוון המשק

כיום, בעל הנחלה כ"בר-רשות" זכאי לבניה של שתי בתי מגורים בגודל 160 כ"א + יחידה להורים בגודל 55 מ"ר, סה"כ 375 מ"ר, במידה ובעל המשק רכש מטרים נוספים בעבר לטובת הבתים הקיימים בנחלה הם יתווספו לסל הזכויות. על זכויות אלו חלות דרישה רצף בין דורי ומעמדו בזכויות אלו הוא כבר-רשות. רמ"י מאפשרים לבעל הנחלה לעגן ולרכוש את זכויות במשק ובעצם לעבור מבר-רשות למעמד של חוכר בנחלה שלו. ההיוון מתבצע על חלקת המגורים בהתאם לתב"ע הקיימת עד מגבלת 2.5 דונם.
בהתאם לכך מוצעים שני מסלולי כניסה להסדר:

מסלול דמי חכירה – 3.75%

במסלול זה, בעל הנחלה רוכש ומעגן את זכויותיו הבסיסיות שהוענקו לו עם קבלת הנחלה. כלומר לא נוצרות זכויות חדשות מעבר לקיים, אך נוצרות יותר אפשרויות לבעל הנחלה עם אותן זכויות. אז מה נקבל במסלול זה?

-כאשר ניכנס למסלול זה בעל הנחלה רוכש את זכויות הבניה הבסיסיות שקיבל, כך שהוא יכול להשתמש **ב375** מ"ר כרצונו ולייעד אותן בין היחידות השונות. לדוגמא, בנית יח"ד אחת בגודל 375 מ"ר **ללא תשלום דמי היתר**.

-בנוסף, בעל הנחלה מקבל **פטור** מהדרישה לרצף בין דורי בנחלה.

- לאחר כניסה למסלול ההיוון ניתן להקים בית שלישי בנחלה (לא ניתן לעשות ללא היוון)

- לאחר הכניסה להסדר יכול בעל המשק לבצע פיצול נחלה, בהשלמה ל-33% משווי **המגרש המפוצל**, כאשר ללא כניסה להסדר הדבר לא אפשרי.

- בעל הנחלה הופך לחוכר וחותם על חוזה חכירה עם הזכויות שפורטו מעלה.

עלות מוערכת של דמי החכירה בכניסה להסדר: כ- 380,000 ₪
יש להוסיף תשלום מס רכישה כחוק.

הערה: נכון למועד הבדיקה, לא קיים תצ"ר עדכני לנחלה, לפני ביצוע עסקה מול רמ"י יש לבצע תצ"ר עדכני.

BoosT
החברה לפיתוח נכסים

סטטוס קיים במשק

בהיתר
הגשת תוכניות הסדרה
להריסה/ הסדרה

1. בית מגורים ראשון + רביעי
1.1. ממ"ד
1.2. מחסן
1.3. חניה
2. בית מגורים רביעי
3. בריכה
4. בית מגורים שני (מגרש השלמה)

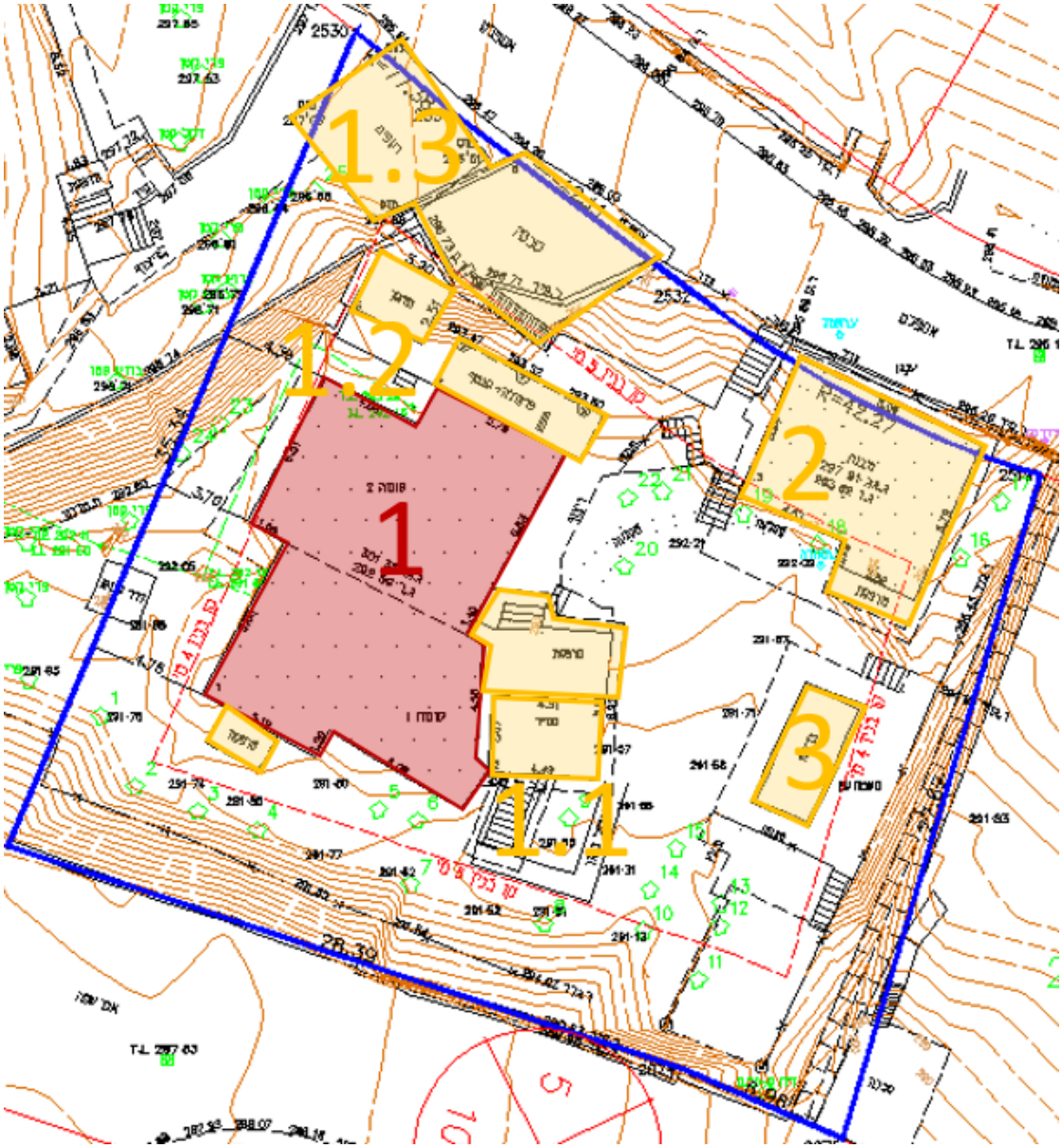

רח' הניר 1, אזור התעשייה באר טוביה | TEL: 03-3816363
info@boost-k.com

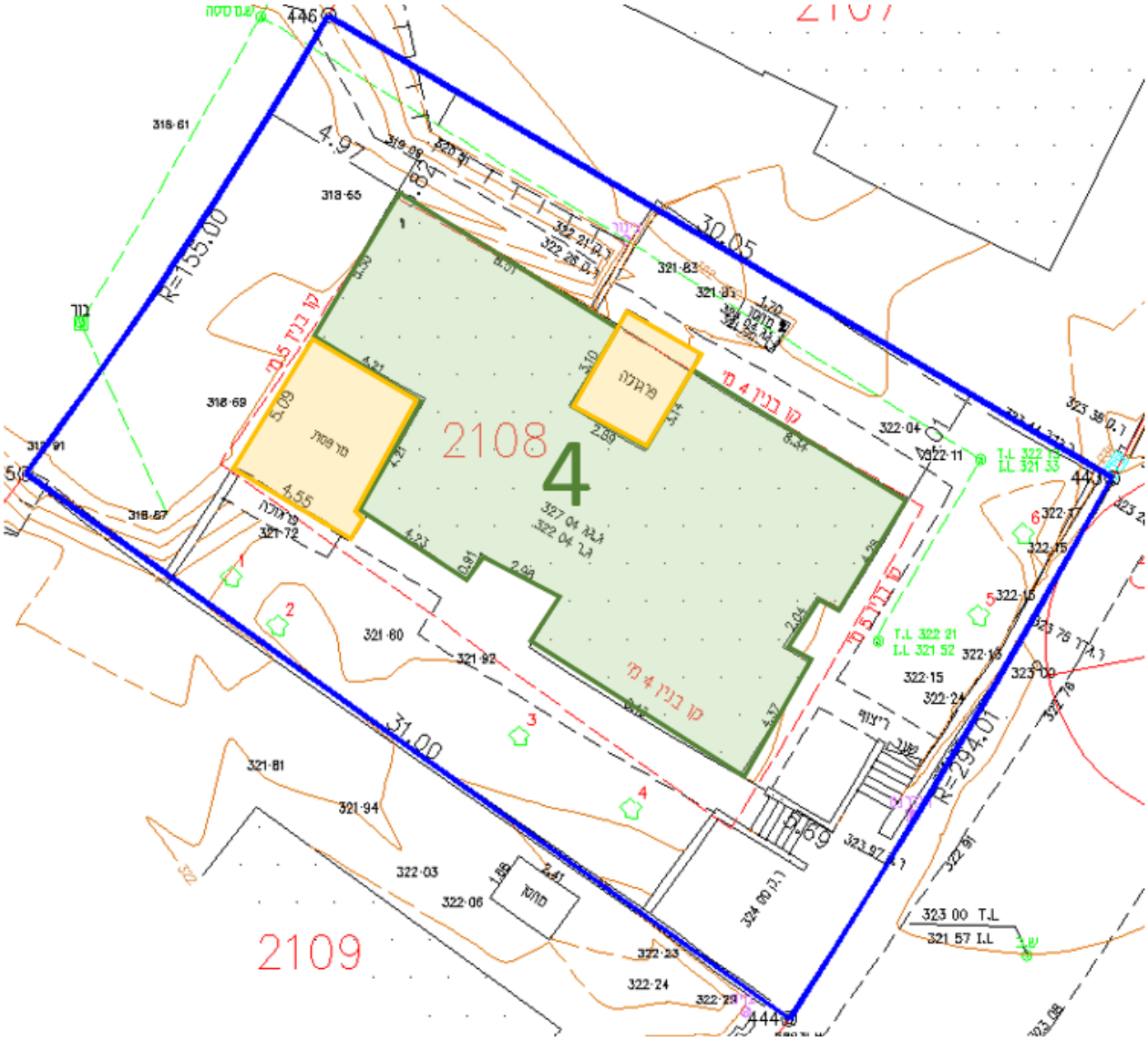
2108
4
2109
R=155.00
R=294.01
30.05
31.00
4.97
קו בניין 4 מ'
קו בניין 5 מ'
מרפסת
מרפסת
מרפסת
מרפסת
T.L 322 21
I.L 321 52
323 00 T.L
321 57 I.L

מתווה הסדרה

מבנה 1 - בית מגורים ראשון + רביעי:

סטטוס: לאחר בדיקת מפת המדידה בשילוב הלווין ואפיון המבנה עם מזמיני הבדיקה, נמצא ששטחי המגורים במבנה מגיעים לגודל של כ-**216 מ"ר** (מ.תחתון 74, מ.ע 142) + פרגולות כ- **44 מ"ר**.

בפועל המבנה מחולק ל-2 בתי מגורים כדלהלן:

בית מגורים ראשון: בשטח של כ-**142 מ"ר** (מפלסים עליונים).

בית מגורים רביעי: בשטח של כ- **74 מ"ר** (מפלס תחתון).

למבנה קיים היתר משנת 1981 המתיר בית מגורים **אחד** בגודל של **90.07 מ"ר** + מקלט **13.44 מ"ר** במפלס התחתון שלא נכלל בטבלת השטחים. המבנה חורג מקו בניין צידי.

השלכות: בית המגורים עומד לא בהתאם להיתר שכן נעשו בו שינויים כמתואר בעמוד הבא. עיקר השינויים נובעים מהרחבת המבנה בשטח של כ- 61 מ"ר במפלס התחתון ובשטח של כ-52 מ"ר במפלס העליון המסומנים בצהוב מלא, מהקמת פרגולות בשטח של כ- 44 מ"ר המסומנים בצהוב מקוקו ומעבירת שימוש והסבת שטח המפלס התחתון לבית מגורים שלישי. על כן קיימת חשיפה לדמי שימוש בגין שטח בית המגורים הרביעי המוערכים בכ- 25,000 ₪ לכל שנה עד 7 שנים אחורה ובסה"כ כ-175,000 ₪. יש להתאים את המבנה להיתר או להסדירו כמפורט בהמשך.

מפלס תחתון (בית שלישי):

מופיע בהיתר אך לא נבנה

בנוי אך לא מופיע בהיתר

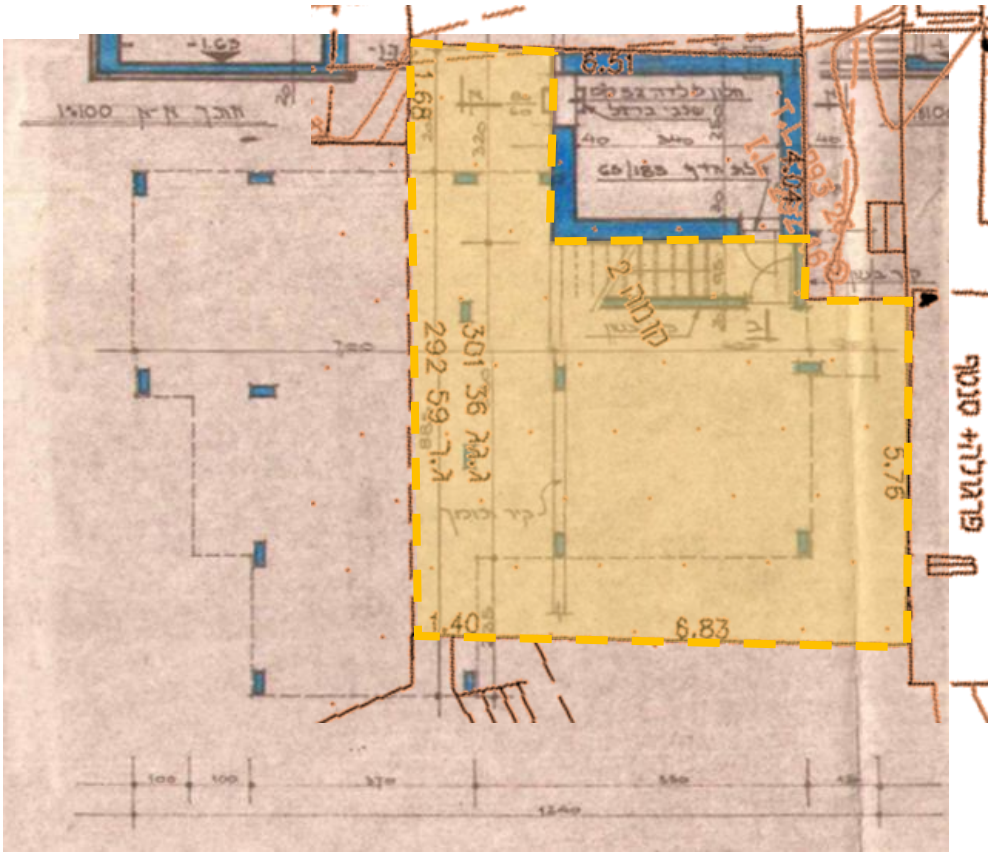

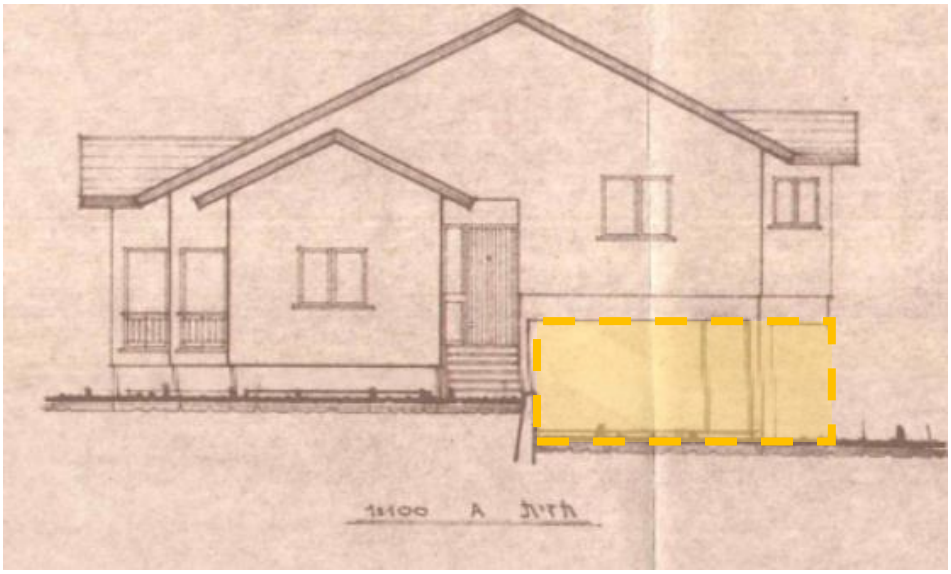

מפלס עליון (בית ראשון):

אפשרויות הסדרה:

<u>אפשרות ראשונה – הסדרת המבנה כבית מגורים ראשון</u>

קיימת אפשרות להסדיר את המבנה כבית אחד בגודל 200 מ"ר עיקרי ושירות ללא מרתף (בית ראשון). בעת הסדרת המבנה כאמור יחול תשלום דמי היתר בעבור השטח העולה על 160 מ"ר. דמי היתר מוערכים בכ- 6,800 ₪ למ"ר עיקרי ובכ- 3,400 ₪ למ"ר שירות נכון לתאריך הבדיקה ובסה"כ כ -270,000 ₪ בעבור 40 מ"ר (ללא הפרגולות). יש לקחת בחשבון כי באפשרות זו יש לבצע הריסות בפועל ולהתאים את הבית לגודל של 200 מ"ר סה"כ.

סה"כ – דמי היתר 270,000 ₪.

<u>אפשרות שניה – הסדרת המבנה כבית מגורים ראשון + בית מגורים שלישי</u>

קיימת האפשרות להסדיר את המבנה כבית מגורים ראשון בשטח 160 מ"ר + בית מגורים שלישי בשטח 56 מ"ר. בכדי להסדיר בית מגורים שלישי בנחלה יש להצטרף לאחד ממסלולי ההיוון המפורטים בבדיקה. מכיוון שבית המגורים השלישי עומד ושלא כדין, בעת הסדרתו יחול תשלום דמי היתר החל מהמ"ר הראשון המוערך בכ- 6,800 ₪ למ"ר עיקרי ובכ- 3,400 ₪ למ"ר שירות נכון לתאריך הבדיקה ובסה"כ כ- 380,000 ₪.

סה"כ – היוון 380,000 ₪ + דמי היתר 380,000 ₪.

<u>אפשרות שלישית – הסדרת המבנה כבית מגורים ראשון + יחידה צמודת קיר</u>

קיימת האפשרות להסדיר את המבנה כבית מגורים ראשון בשטח 166 מ"ר + יחידה צמודת קיר בשטח 50 מ"ר. כפי שנמסר לנו ממזמיני הבדיקה, בנחלה לא קיים רצף בן דורי, על כן בכדי להסדיר יחידה צמודת קיר יש להצטרף לאחד ממסלולי ההיוון המפורטים בבדיקה.

הסדרת המבנה כאמור תהיה כרוכה בתשלום דמי היתר בגין שטח המבנה הראשון העולה על 160 מ"ר, כלומר בעבור 6 מ"ר המוערכים בכ- 41,000 ₪, וכן בתשלום דמי היתר בגין שטח היחידה צמודת הקיר המוערכים בכ- 340,000 ₪.

סה"כ ללא רצף בן דורי – היוון 380,000 + דמי היתר 381,000 ₪.

יש לקחת בחשבון שיידרש פתרון מיגון במסגרת ההסדרה של הבית בכל אחת מן האפשרויות.

בכל אחת מהאפשרויות אנו ממליצים להחליף את קירוי הפרגולות לסנטף שקוף

המבנה חורג מקו בניין צידי. ניתן לראות כי בהיתר הבניה המבנה מצוי במרחק של 4 מ' מגבול המגרש ואילו במפת המדידה מרחקה המבנה מגבול המגרש הינו 3.7 מ'. אנו סבורים כי ניתן לטעון שחריגה זו אינה נובעת מתוספת בניה, אלא שייכת למבנה המקורי המופיע בהיתר ובסה"כ זז מעט מיקומו. וסבורים כי חריגה זו אינה תהווה חסם להסדרת המבנה.

חשוב לציין כי קיימת חשיפה לכך שהוועדה המקומית תדרוש את הסדרת המבנה במסגרת קווי הבניין. במצב נ"ל בכדי להסדיר את המבנה יש להרוס את החלק החורג מקו הבניין או לחלופין להגיש תב"ע נקודתית לתיקון קווי הבניין.

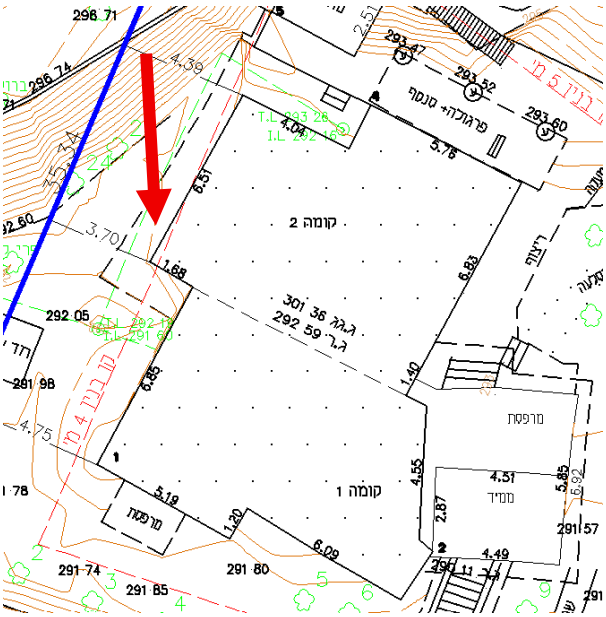

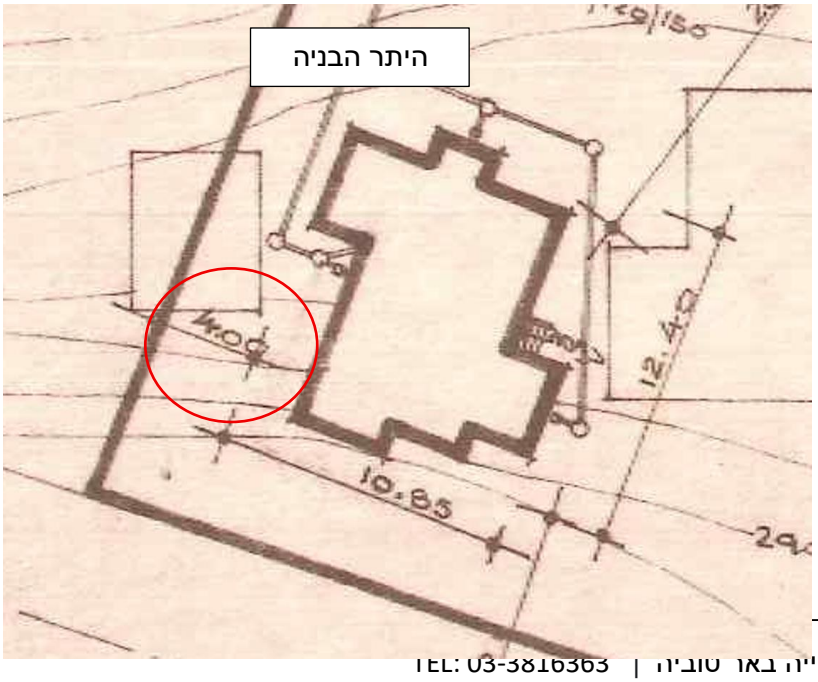

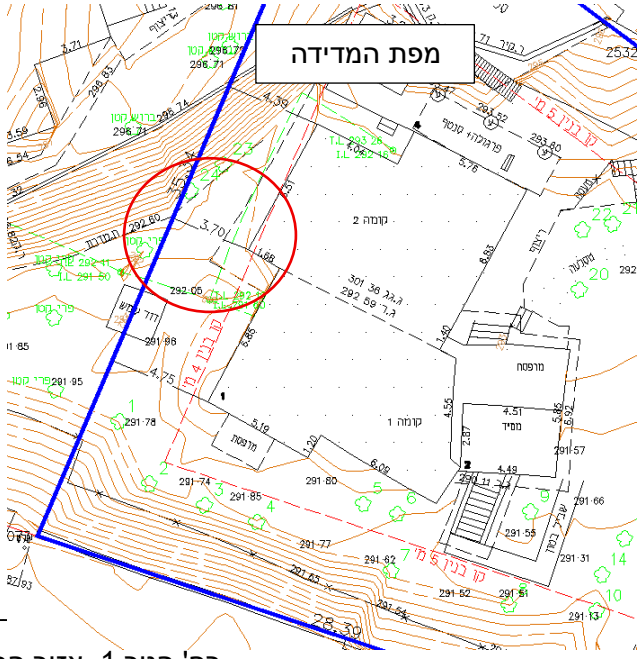

מבנה 1.1 – ממ"ד:

סטטוס: לאחר בדיקת מפת המדידה בשילוב הלוויין, נמצא ששטח המבנה מגיע לגודל של כ- **14 מ"ר**. לא נמצא כל היתר למבנה.

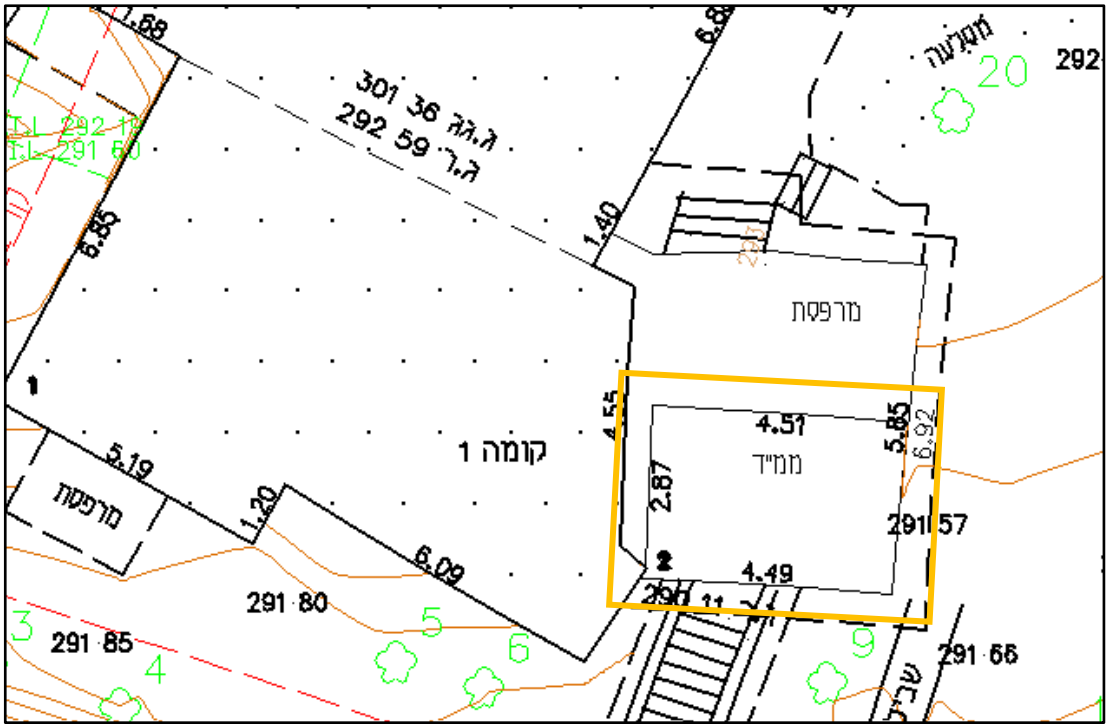

השלכות: המבנה עומד ללא היתר ומהווה שטח שירות לבתי המגורים במשק. לא ייגבו דמי שימוש בגין המבנה. יש להסדיר את המבנה או לפנות אותו.

בכדי להסדיר את המבנה יש להגישו להיתר בניה כשטח שירות לאחד מבתי המגורים במשק. במידה והבית אליו ישוייך יהיה בשטח כולל של 160 מ"ר ומעלה, בעת הסדרת המבנה יחול תשלום דמי היתר המוערך בכ- 3,400 ₪ למ"ר שירות נכון לתאריך הבדיקה ובסה"כ כ- 95,000 ₪.

במידה והבית אליו ישוייך המבנה הינו בית מגורים קיים בהיתר והמבנה יוסדר כממ"ד בצורה אינטגרלית כחלק מהמבנה, הממ"ד יהיה פטור מתשלום דמי היתר.

יש לשים לב כי גודל מירבי שניתן להסדיר בית מגורים הינו 200 מ"ר עיקרי ושירות.

<u>מבנה 1.2 – מחסן:</u>

<u>סטטוס:</u> לאחר בדיקת מפת המדידה בשילוב הלווין, נמצא ששטח המבנה מגיע לגודל של כ- **8 מ"ר**. לא נמצא כל היתר למבנה.

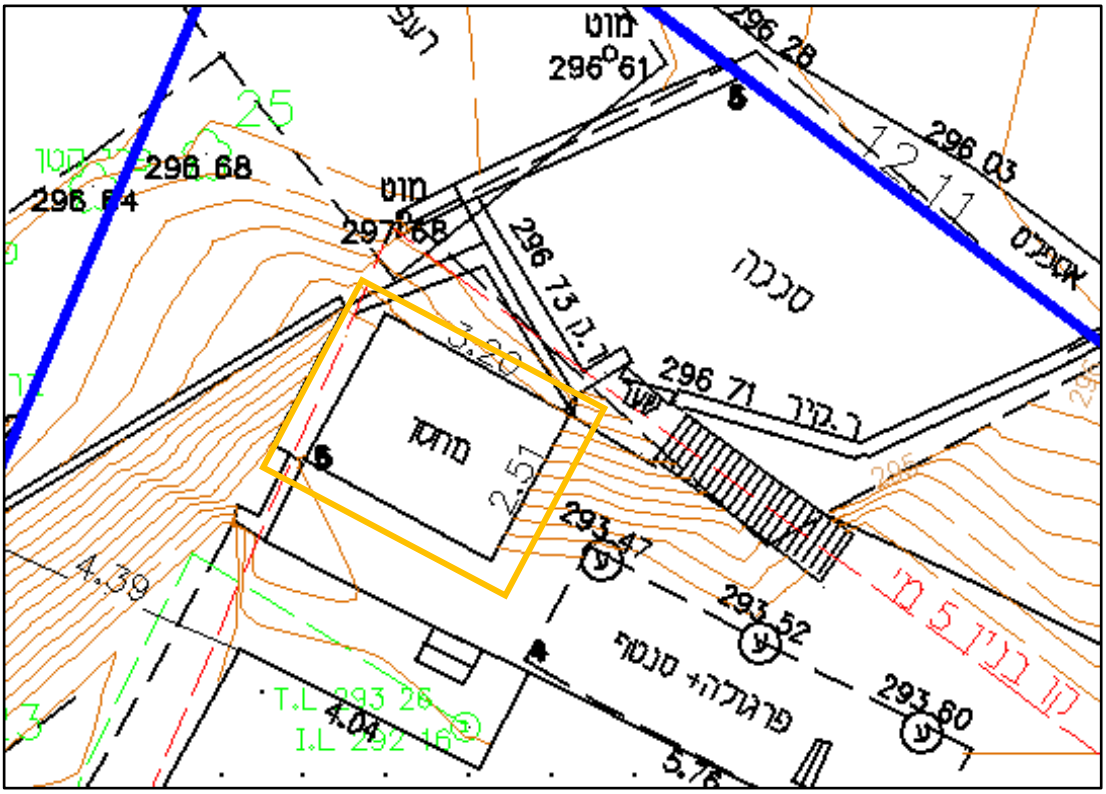

<u>השלכות:</u> המבנה עומד ללא היתר ומהווה שטח שירות לבתי המגורים במשק. על כן קיימת בגינו חשיפה לדמי שימוש המוערכים בכ- 1,400 ₪ לכל שנה עד 7 שנים אחורה ובסה"כ כ- 9,800 ₪. יש להסדיר את המבנה או לפנות אותו.

בכדי להסדיר את המבנה יש להגישו להיתר בניה כשטח שירות לאחד מבתי המגורים במשק. במידה והבית אליו ישוייך יהיה בשטח כולל של 160 מ"ר ומעלה, בעת הסדרת המבנה יחול תשלום דמי היתר המוערך בכ- 3,400 ₪ למ"ר שירות נכון לתאריך הבדיקה ובסה"כ כ- 27,000 ₪.

יש לשים לב כי גודל מירבי שניתן להסדיר בית מגורים הינו 200 מ"ר עיקרי ושירות.

מבנה 1.3 – חניה:

סטטוס: לאחר בדיקת מפת המדידה בשילוב הלוויין, נמצא ששטח המבנה מגיע לגודל של כ- **70 מ"ר**. לא נמצא כל היתר למבנה. המבנה חורג מגבול מגרש.

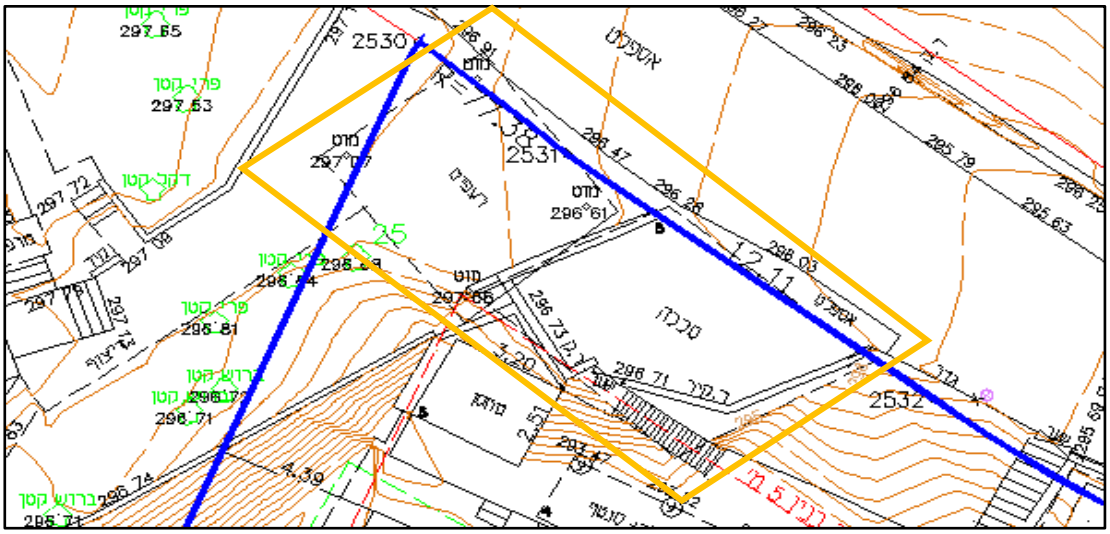

השלכות: המבנה עומד ללא היתר ומהווה שטח שירות לבתי המגורים במשק. על כן קיימת בגינו חשיפה לדמי שימוש המוערכים בכ- 12,000 ₪ לכל שנה עד 7 שנים אחורה ובסה"כ כ- 84,000 ₪. יש להסדיר את המבנה או לפנות אותו.

המבנה חורג מגבול מגרש ומקווי בניין. בכדי להסדיר את המבנה ראשית יש להרוס את החלק החורג מגבול המגרש. לאחר מכן יש להגיש את המבנה להיתר בניה כשטח שירות לאחד מבתי המגורים במשק שכן אין מניעה להקמת חניות בקו בניין צידי וקדמי 0.

במידה והבית אליו ישוייך יהיה בשטח כולל של 160 מ"ר ומעלה, בעת הסדרת המבנה יחול תשלום דמי היתר המוערך בכ- 3,400 ₪ למ"ר שירות נכון לתאריך הבדיקה ובסה"כ כ- 238,000 ₪. אנו ממליצים להחליף את קירוי המבנה לסטנף שקוף ובכך להימנע מהסדרתו ואף מתשלום דמי היתר בעבורו במידת הצורך.

בניית חניות בקו בניין RE: 0

AE Ariel Eliyahu <ariel@m-yehuda.org.il>
אל Roi Boost

אין מניעה

בברכה,

אריאל אליהו - מידען
משרד: 02-9958921
מייל: ariel@m-yehuda.org.il

הי אריאל מה המצב,

רציתי לוודא הם ניתן להקים חניות בקו בניין קדמי וצידי 0 בנחלות במושב מסילת ציון ?

<u>מבנה 2 - בית מגורים שלישי:</u>

<u>סטטוס:</u> לאחר בדיקת מפת המדידה בשילוב הלוויין, נמצא ששטחי המגורים בבית מגיעים לגודל של כ- **55 מ"ר**. המבנה עומד ללא היתר. המבנה חורג מגבול מגרש קדמי ומקווי בניין.

<u>השלכות:</u> בית המגורים עומד ללא היתר ומהווה בית מגורים שלישי בנחלה. על כן קיימת חשיפה לדמי שימוש המוערכים בכ- 19,000 ₪ לכל שנה עד 7 שנים אחורה ובסה"כ כ- 133,000 ₪. יש להסדיר את המבנה או לפנות אותו.

המבנה חורג מגבול מגרש קדמי ומקווי בניין. בכדי להסדיר את המבנה כבית שלישי (בהנחה כי לא הוסדר בית שלישי אחר במשק), ראשית יש להרוס את החלק החורג מגבול המגרש. לאחר מכן יש להרוס את החלקים החורגים מקו הבניין / למקם את הבית במסגרת קווי הבניין או לחלופין להגיש תב"ע נקודתית לתיקון קווי הבניין בצורה שתכלול את המבנה בתוכם.

לאחר מכן יש להיכנס לאחד ממסלולי ההיוון המפורטים בבדיקה ולהגישו להיתר בניה. מכיוון שבית המגורים עומד ושלא כדין, בעת הסדרתו יחולו דמי היתר החל מהמ"ר הראשון המוערכים בכ-6,800 ₪ למ"ר עיקרי ובכ-3,400 ₪ למ"ר שירות נכון לתאריך הבדיקה ובסה"כ כ- 375,000 ₪. יש לקחת בחשבון שיידרש פתרון מיגון במסגרת ההסדרה של הבית.

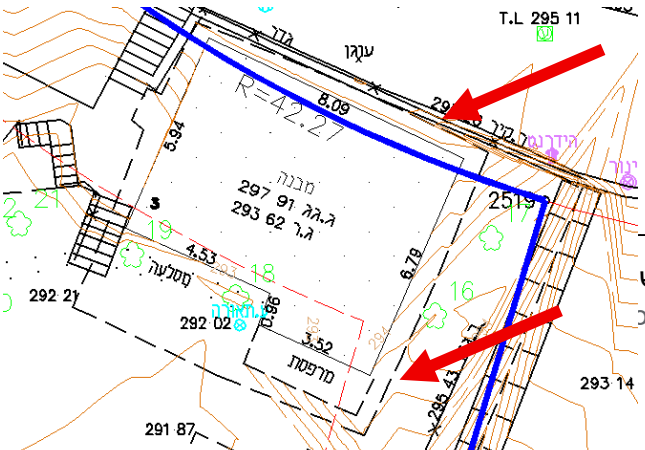

מבנה 3 – בריכה:

סטטוס: לאחר בדיקת מפת המדידה בשילוב הלווין, נמצא ששטח המבנה מגיע לגודל של כ- **13 מ"ר**. לא נמצא כל היתר למבנה. הדק המוגבה שמסביב לבריכה חורג מקו בניין.

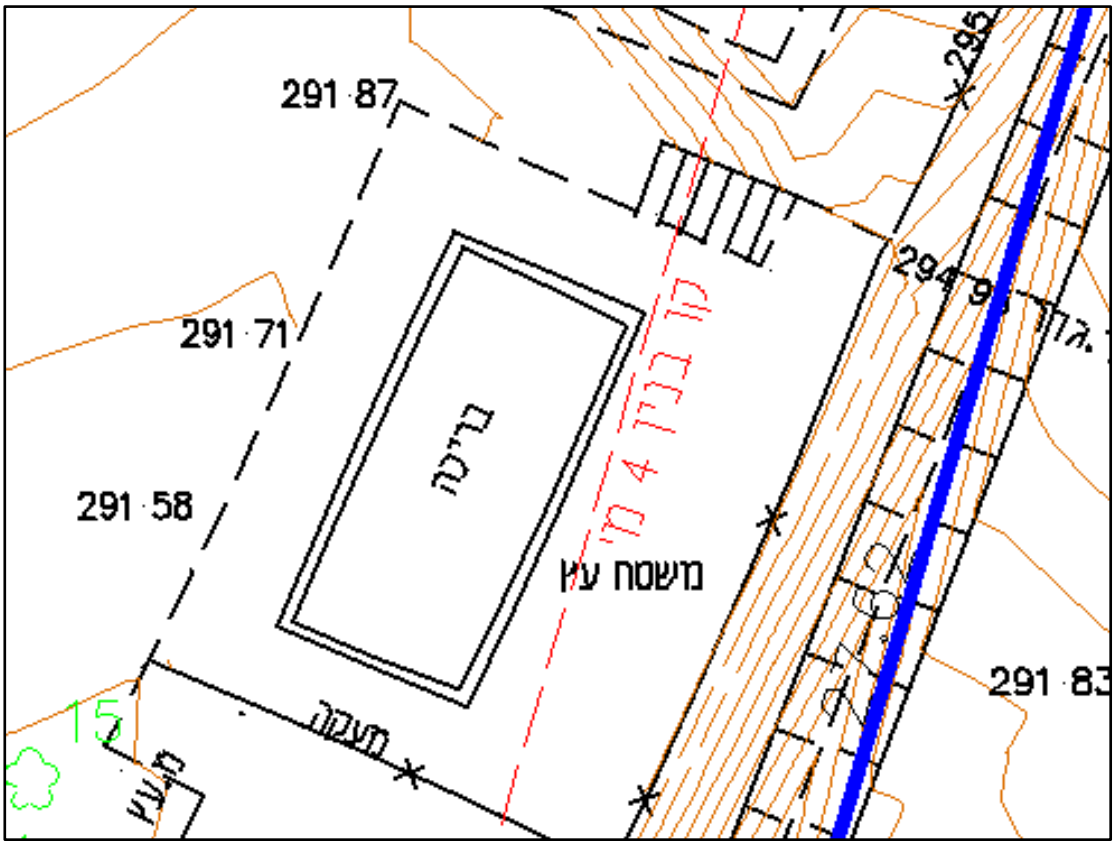

השלכות: המבנה עומד ללא היתר ומהווה בריכת שחיה פרטית במשק. לא ייגבו כל דמי שימוש בגין המבנה. יש להסדיר את המבנה או לפנות אותו.

הדק המוגבה שמסביב לבריכה חורג מקו בניין. בכדי להסדיר את המבנה יש להרוס את החלק החורג מקו הבניין או לחלופין להגיש תב"ע נקודתית לתיקון קווי בניין בצורה שתכלול את הדק בתוכה.

לאחר מכן יש להגיש את המבנה להיתר בניה. הסדרת המבנה כאמור תהיה כרוכה בתשלום דמי היתר המוערך בכ- 2,300 ₪ לכל מ"ר ובסה"כ כ- 30,000 ₪ בעבור 13 מ"ר.

במידה ויפורק כל חלק הדק המוגבה ותשאר בריכת אינטקס ללא הגבהה, הבריכה לא תדרש בהסדרה.

מבנה 4 - בית מגורים שני (ממוקם במגרש ההשלמה):

סטטוס: לאחר בדיקת מפת המדידה בשילוב הלווין, נמצא ששטחי המגורים בבית מגיעים לגודל של כ- **167 מ"ר** + פרגולות כ- **32 מ"ר**. למבנה קיים היתר משנת 2008 המתיר בית מגורים בגודל **164 מ"ר** עיקרי + ממ"ד. המבנה חורג מעט מקו בניין צידי.

השלכות: נראה כי בית המגורים עומד בהתאם להיתר למעט שינויים שנעשו בו כמתואר בעמוד הבא. עיקר השינויים נובעים מהקמת פרגולות בשטח של כ-32 מ"ר המסומנים בצהוב מקוקו. קיים פער נוסף זניח של כ-3 מ"ר הנובע מאופן חישוב השטחים המפה אל מול ההיתר. יש להרוס את הפרגולות או להסדירם.

בכדי להסדיר את הפרגולות יש להגישם להיתר בניה כשטח שירות לבית המגורים.
הסדרת הפרגולות כאמור תהיה כרוכה בתשלום דמי היתר במוערך בכ-3,400 ₪ למ"ר שירות נכון לתאריך הבדיקה ובסה"כ כ- 108,000 ₪.

אנו ממליצים להחליף את קירוי הפרגולות לסנטף שקוף ובכך להימנע מהסדרתן ואף מתשלום דמי היתר בעבורן.

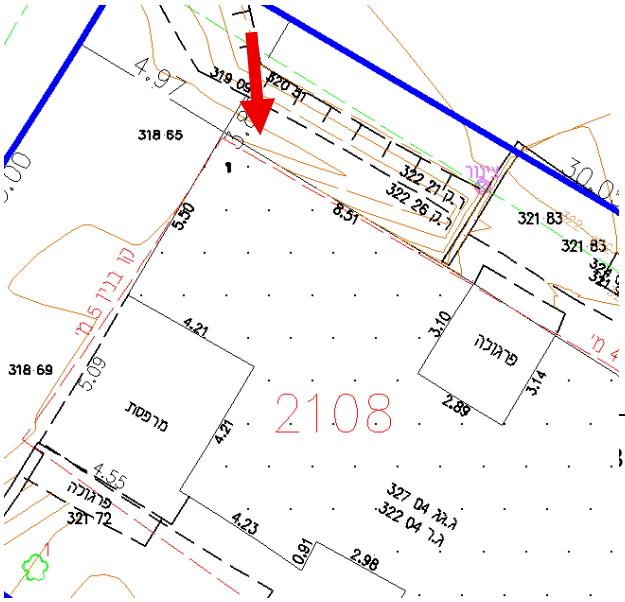

המבנה חורג מעט מקו בניין צידי. אנו סבורים כי חריגה זו לא תהווה חסם לכל הליך במשך. קיימת חשיפה לכך שהוועדה המקומית תדרוש את הסדרת המבנה בגבולות קווי הבניין דבר היצריך את הריסת החלק החורג או הגשת תב"ע נודתית לתיקון קווי בניין.

מופיע בהיתר אך לא נבנה

בנוי אך לא מופיע בהיתר

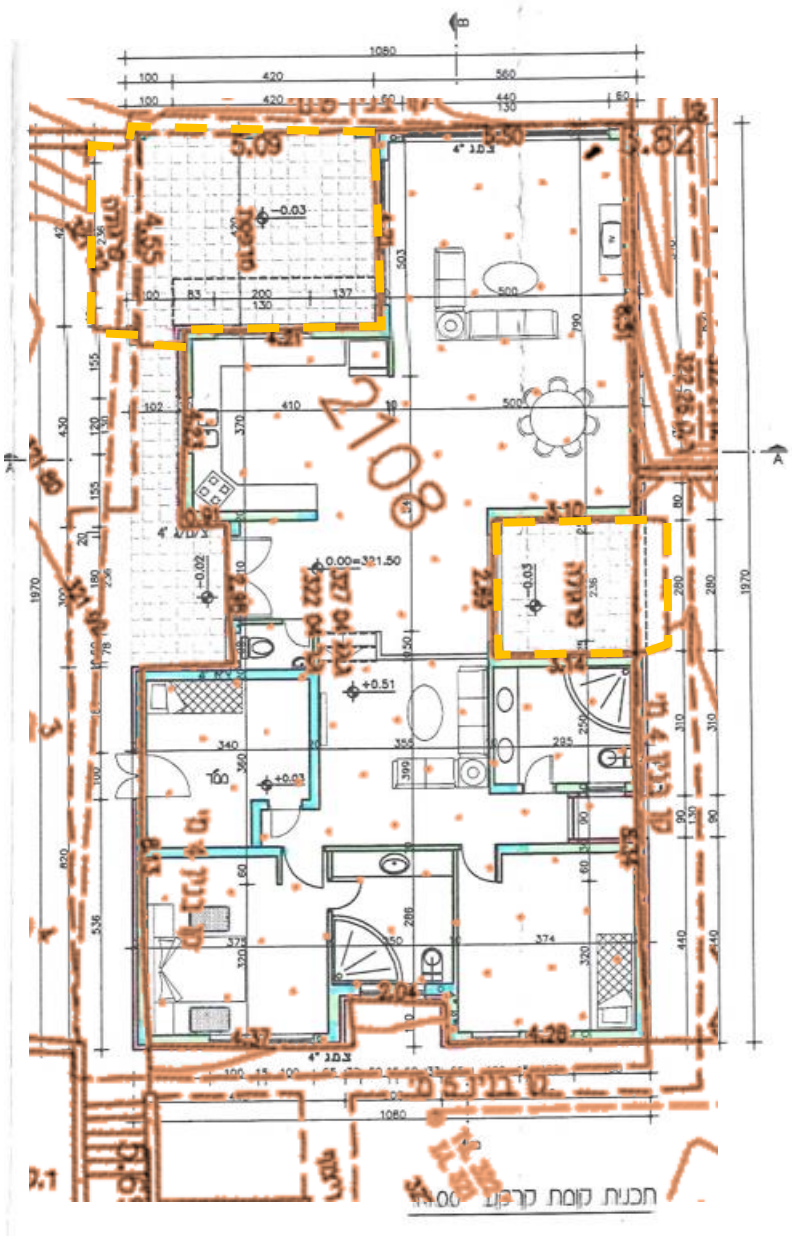

כחלק מבדיקת ההתכנות נתבקשנו לבחון אפשרות להרחבת המבנה הנ"ל. זכויות הבניה במגרש עליו בנוי המבנה (מגרש ההשלמה) הינם לבית מגורים **אחד** בגודל של 200 מ"ר סה"כ (עיקרי ושירות) + 30 מ"ר לחניה מקורה. כלומר לא ניתן יהיה להסדיר יחידת דיור נוספת במגרש.

מכיוון שבית המגורים מגיע כיום לגודל של כ-167 מ"ר, ניתן יהיה להרחיב את בית המגורים הקיים בשטח של עוד כ-33 מ"ר + חניה מקורה בשטח 30 מ"ר. יש לשים לב שהרחבת המבנה יכולה להיעשות רק במסגרת קווי הבניין (למעט החניה). בכדי לבצע הרחבה מעבר לקווי הבניין הנוכחיים, יש להגיש תב"ע נקודתית שתתקן את קווי הבניין.

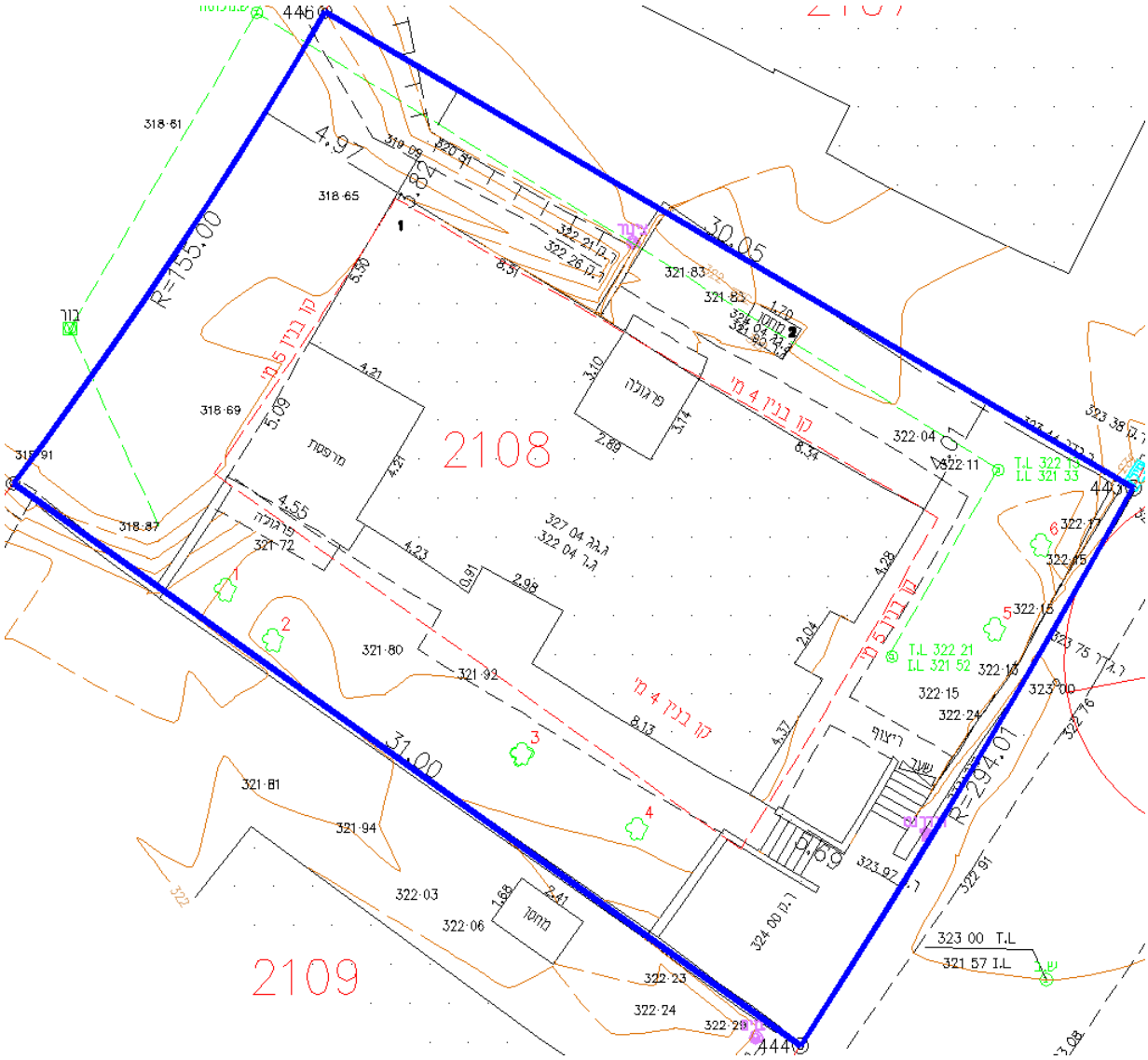

מתווה להקמת בית שלישי

הקמת בית המגורים השלישי תתאפשר רק לאחר הסדרה של המשק וכניסה לאחד ממסלולי החכירה (היוון) שתוארו קודם ולאחר כניסת תב"ע המוסיפה זכות לבית שלישי לתוקף. לאחר הסדרת המצב בנוי (לא כולל פרגולות) וכניסה למסלול בדמי חכירה יחויבו דמי היתר על כל מ"ר מעבר ל-383 מ"ר מכלל מבני המגורים בנחלה (בית ראשון 161, יחידה צמודה 55, בית שני 167).

על הבתים להיבנות בגבולות ה-1.6 דונם (שטח צהוב) שבהם יתכנסו כלל המבנים בחלקת המגורים. – המוצג להמחשה בלבד ואינו בהתאם לגדלים מדויקים.

לאחר הסדרת המצב הקיים והיוון המשק לא ישאר שטח פטור מתשלום דמי היתר וכל מ"ר נוסף יחויב בתשלום דמי היתר המוערכים בכ-6,800 ₪ למ"ר עיקרי ובכ- 3,400 ₪ למ"ר שירות.

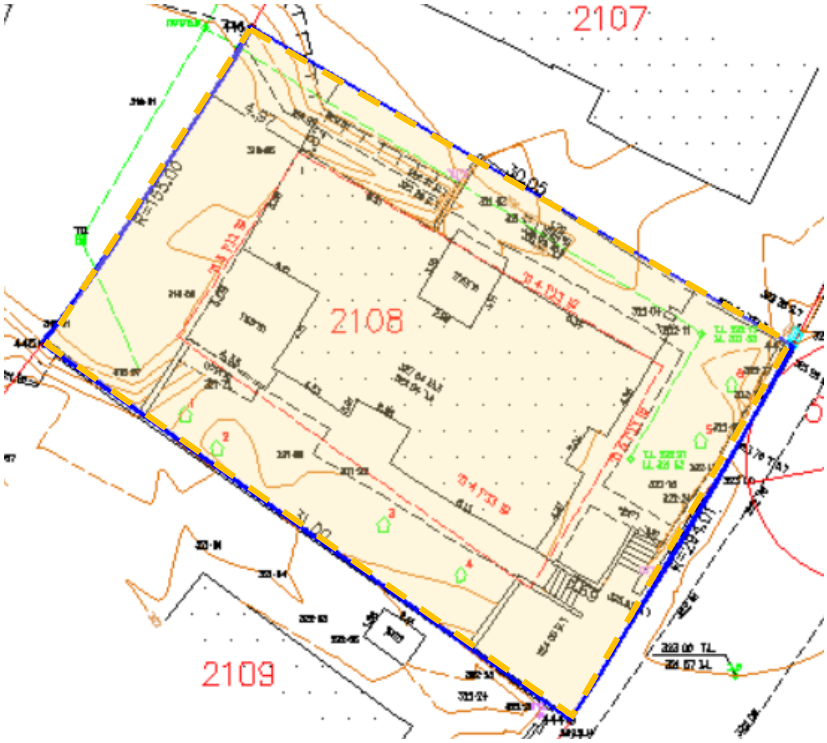

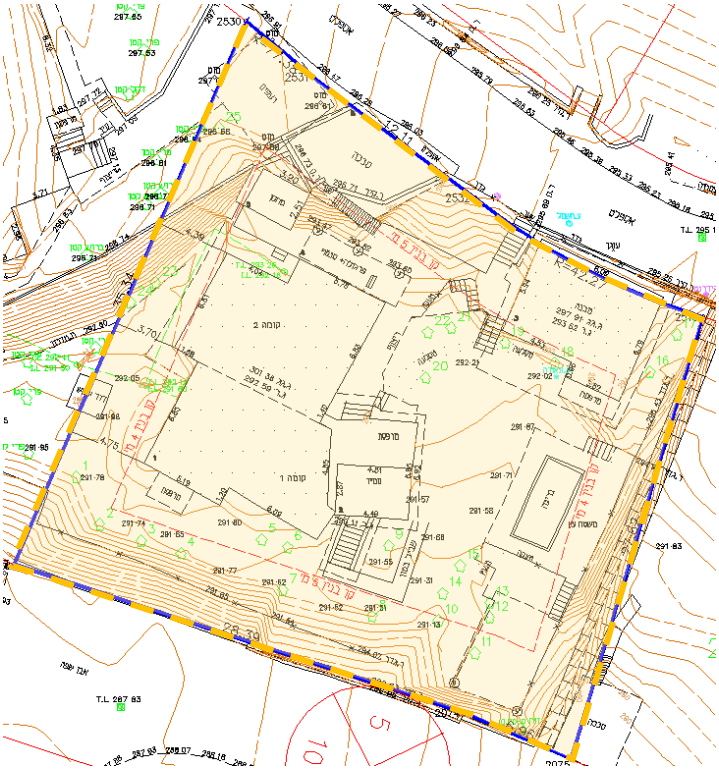

מתווה להקמת פל"ח

כחלק מבדיקת ההתכנות הועלתה האפשרות להקמת מבני פל"ח בנחלה. בכדי להקים מבנה פל"ח או להסדיר מבנה קיים יש להגיש היתר בניה שיכלול תשלום דמי היתר לרמ"י בהתאם לשימוש שייבחר למבנה.

חשוב לציין כי לאחר בדיקה מול אריאל מהוועדה המקומית שימושי הפל"ח היחידים המותרים הם במסגרת התב"ע החדשה המגדירה זכויות לתיירות כפרית בלבד.

בהתאם לשימושים המותרים בתב"ע, יהיה ניתן להקים מבנים לפעילות צימרים תחת הגדרת תיירות כפרית במסגרת פל"ח ובהיקף של עד 350 מ"ר בסה"כ - כאשר גודל כל צימר נע בין 20-55 מ"ר. דמי היתר לצימרים מוערכים בכ- 2,500 ₪ לכל מ"ר. על הסכומים הנ"ל יש לקחת מס רכישה כחוק. יש לקחת בחשבון כי בעת הקמת מבני פל"ח יידרש פתרון מיגון.

צימרים סה"כ עד 350 מ"ר גודל צימר 20-55 מ"ר ונגזרת מכך מספר יחידות הקייט כפף כמובן לאישור משרד התיירות וחיבור לביוב מרכזי

בברכה,

אריאל אליהו - מידען
משרד: 02-9958921
מייל: ariel@m-yehuda.org.il

מועצה אזורית מטה יהודה בלב המדינה | דברו איתנו:

נספח גדלי מבנים בהתאם להיקף חקלאות

שטחי מבנים חקלאיים (מ"ר) - גידולים צימחיים

הענף	סוג הגידול	מיקום כללי	מיקום במשק משפחתי	גודל שטח מעובד	שטח אריזה ומיון	שטח קירור	שטח מחסן שירות	שירותים, מקלחות, חדר אוכל ומטבח	סככת ציוד וכלים חקלאיים	ס"ה שטח	הערות
מטעים	נשירים וסובטרופים	שטח מבונה	חלקה א	20 עד 150 דונם	320	100	100	60	150	730	
	נשירים וסובטרופים	שטח מבונה	חלקה א	150 עד 300 דונם	380	100	100	60	250	890	
	בשטח פתוח	שטח פתוח	גם חלקה ב וג	מעל 40 ד'	0	0	0	0	250	250	מפולשת. מחסן 20 מ"ר כחלק מהסככה.
	כרם מאכל	שטח מבונה	חלקה א	20 עד 150 דונם	300	100	100	60	150	710	
	כרם מאכל	שטח מבונה	חלקה א	150 עד 300 דונם	470	100	100	60	250	980	
	כרם מאכל	שטח פתוח	גם חלקה ב וג	מעל 60 ד'	0	0	0	0	250	250	מפולשת. מחסן 20 מ"ר כחלק מהסככה.
	כרם יין	שטח מבונה	חלקה א	20 עד 100 דונם	0	0	100	60	40	200	
	כרם יין	שטח מבונה	חלקה א	מעל 100 ד'	0	0	100	60	160	320	
	כרם יין	שטח פתוח	גם חלקה ב וג	מעל 60 ד'	0	0	0	0	250	250	מפולשת. מחסן 20 מ"ר כחלק מהסככה.
	בננות	שטח מבונה	חלקה א	20 עד 150 דונם	360	100	100	60	150	770	
	בננות	שטח מבונה	חלקה א	150 עד 300 דונם	360	100	100	60	250	870	
	בננות	שטח פתוח	גם חלקה ב וג	מעל 150 ד'	0	0	0	0	250	250	מפולשת. מחסן 20 מ"ר כחלק מהסככה.
	שקדים	שטח מבונה	חלקה א	מינימום 50 ד'	0	0	100	0	150	250	
	שקדים	שטח פתוח	גם חלקה ב וג	מעל 50 ד'	0	0	0	0	150	150	מפולשת. מחסן 20 מ"ר כחלק מהסככה.
	זיתים	שטח מבונה	חלקה א	מינימום 50 ד'	0	0	100	0	150	250	
	זיתים	שטח פתוח	גם חלקה ב וג	מעל 50 ד'	0	0	0	0	150	150	מפולשת. מחסן 20 מ"ר כחלק מהסככה.
	הדרים	שטח מבונה	חלקה א	מינימום 50 ד'	300	110	100	60	150	720	
	הדרים	שטח מבונה	חלקה א	50 עד 180 דונם	450	200	100	60	150	960	
	הדרים	שטח פתוח	גם חלקה ב וג	אין בניה	0	0	0	0	0	0	
	תמרים, תאנים, שסק וכו'	שטח מבונה	חלקה א	20 עד 150 דונם	320	100	100	60	150	730	
	תמרים, תאנים, שסק וכו'	שטח פתוח	גם חלקה ב וג	אין בניה	0	0	0	0	0	0	
ירקות	פלפל	שטח מבונה	חלקה א	20 עד 50 ד'	400	60	100	60	150	770	
	פלפל	שטח מבונה	חלקה א	50 עד 150 דונם	600	80	100	60	250	1,090	
	מלונים	שטח מבונה	חלקה א	20 עד 50 ד'	400	60	100	60	150	770	
	מלונים	שטח מבונה	חלקה א	50 עד 150 דונם	600	80	100	60	250	1,090	
	עגבניות שרי	שטח מבונה	חלקה א	20 עד 50 ד'	300	60	100	60	150	670	
	עגבניות שרי	שטח מבונה	חלקה א	50 עד 150 דונם	500	80	100	60	250	990	
	תבלינים טריים	שטח מבונה	חלקה א	10 עד 30 דונם	300	80	100	60	150	690	
	תבלינים טריים	שטח מבונה	חלקה א	30 עד 150 דונם	500	120	100	60	150	930	

שטחי מבנים חקלאיים (מ"ר) - גידולים צימחיים

הענף	סוג הגידול	מיקום כללי	מיקום במשק משפחתי	גודל שטח מעובד	שטח אריזה ומיון	שטח קירור	שטח מחסן שירות	שירותים, מקלחות, חדר אוכל ומטבח	סככת ציוד וכלים חקלאיים	ס"ה שטח	הערות
ירקות	ירקות אחרים	שטח מבונה	חלקה א	20 עד 50 ד'	300	60	100	60	150	670	
	ירקות אחרים	שטח מבונה	חלקה א	50 עד 150 דונם	500	80	100	60	250	990	
	פטריות	שטח מבונה	חלקה א		400	0	0	0	0	400	
	תות שדה	שטח מבונה	חלקה א	10 עד 50 דונם	100	20	60	60	150	390	
	כללי	שטח פתוח	גם חלקה ב וג	מינימום 50 ד'	0	0	20	0	100	120	
	תות שדה	שטח פתוח	גם חלקה ב וג	מינימום 20 ד'	0	0	0	0	150	150	מפולשת. מחסן 20 מ"ר כחלק מהסככה.
פרחים	פרחים	שטח מבונה	חלקה א	10 עד 30 דונם	240	60	100	60	150	610	
		שטח מבונה	חלקה א	30 עד 100 דונם	500	60	100	60	150	870	
		שטח פתוח	גם חלקה ב וג	אין בניה	0	0	0	0	0	0	
דבש	מכון רדיה	שטח מבונה	חלקה א	3,500 כוורות	340		100	60	500	1,000	תתאפשר גמישות בין סככות ציוד וכלים חקלאיים לשטחי אריזה ומיון (ניתן להמיר לשטח קירור עד 250 מ"ר מהיקף השטח הכולל).
שחת, קש	מתבן לאחסנת תוצרת	שטח מבונה	חלקה א							1,000	גודל המבנה ייקבע בהתייעצות עם מדריך שה"מ
ח. צמחית	מחסן חקלאי בסיסי	שטח מבונה	חלקה א	מינימום 7 דונם ועד 19 דונם	0	0	40	0	60	100	ניתן להגדיל את גודל הסככה המפולשת (סככת ציוד וכלים חקלאיים) עד להיקף של 110 מ"ר (סה"כ 150 מ"ר).
קנאביס רפואי	קנאביס רפואי - מבנה לטיפול ראשוני, אריזה ומיון.	שטח מבונה	חלקה א'/שטח למבני משק		1720	60	100	60	60	2,000	תתאפשר גמישות בחלוקת גדלים אחרת בין השימושים השונים.
		שטח פתוח	חלקה ב/ג		530	60	40	60	60	750	תתאפשר גמישות בחלוקת גדלים אחרת בין השימושים השונים.

הערות

1. יש לראות בנתוני הטבלה המלצות מקצועיות על פיהן ניתן לקבוע את המלצת המשרד ביחס לגודל מבנה.
2. גודל שטח מעובד הינו טווח המאפשר להמליץ על היקף בינוי נדרש ולא בהכרח את המקסימום האפשרי.
3. מדובר בסדרי גודל. תתאפשר גמישות במידה וקיימים נתונים מקצועיים המצדיקים שינוי הנתון.
4. על מנת לתמוך בשינויים אלה נדרשת חוות דעת מדריך מקצוע ובלבד ששינוי המסגרת לא יחרוג מתוספת של 30%.
5. גודל מתבן לאחסנת תוצרת לא יעלה על 1,000 מ"ר ויקבע בהתאם להיקף הגידול ולצורך אחסנת תוצרת מקומית בלבד.
6. גידול קנאביס במבנה מבוקר (Indoor) יתאפשר רק מתוקף תכנית מפורטת (תב"ע), או בשטח בייעוד מבני משק, או כחלק ממבנה קיים ומאושר לטיפול בתוצרת חקלאית בייעוד חקלאי בחלקה א' או בייעוד מבני משק לאחר הוכחת גידול בחממות.

שטחי מבנים חקלאיים (מ"ר) בעלי חיים

הענף	סוג המבנה הנדרש	יחידת מידה	שטח ליחידה	הערות כלליות
רפת בקר לחלב	כל המבנים - מפתח כללי כולל כל המבנים לרבות מתבן, מאצרה וכו'	חולבת	60	היקף הגידול נמדד לפי מספר החולבות והעדר כולל חולבות ועגלים מתוצרת הרפת. גידול עגלים מחושב בנפרד. ניתן להמליץ על תוספת של 30% עבור סככות לשירות גידול עתידי במידת הצורך.
שטח מבנים וסככות כולל	סככות, מעברים, מבני שירות, יונקיה	מ"ר לכל חולבת	36	
עד 100 פרות	מכון חליבה, חצר המתנה ומבני שירות	מ"ר	410	
מ- 101 עד 300 פרות	מכון חליבה, חצר המתנה ומבני שירות	מ"ר	480	
מ- 301 עד 750 פרות	מכון חליבה, חצר המתנה ומבני שירות	מ"ר	725	
מ- 751 ויותר פרות	מכון חליבה, חצר המתנה ומבני שירות	מ"ר	975	
יונקיה	סככה	מ"ר לכל חולבת	10	
מאצרת זבל	מבנה מקורה	מ"ר לכל חולבת	5	בהתאם לדרישות איכה"ס.
מתבן	מתבן	מ"ר לכל חולבת	3	
עד 100 פרות	מתבן אחד	מ"ר	350	
מ- 101 עד 300 פרות	2 מתבנים - שטח כולל	מ"ר	800	
מ- 301 עד 750 פרות	5 מתבנים - שטח כולל	מ"ר	2,000	
מ- 751 עד 900 פרות	6 מתבנים - שטח כולל	מ"ר	2,400	
בקר לבשר		עגל		
מפטמה בתחום בנוי	שטח שיכון לעגלים	מ"ר לכל עגל	10	גודל עדר מינימלי 100 ראש.
מפטמה בתחום בנוי	מתבן ל-1000 עגלים	מ"ר	500	
בקר במרעה				
בשטח פתוח / בשטחי מרעה	סככה מפולשת	מקסימום - מ"ר	80	גודל עדר מינימלי 100 ראש. ללא סככות גידול.
	מחסן שירות	מקסימום - מ"ר	20	
	מתבן	מקסימום - מ"ר	150	
	מרכז מזון	מקסימום - מ"ר	200	
צאן לחלב בשטח בנוי				אין לאשר בשטח פתוח
צאן לחלב בשטח בנוי	שטח שיכון - סככה וחצר	מ"ר לעז או כבשה חולבת	5	
	שטח שיכון - סככה וחצר	מ"ר לצפירה או שיה	5	
	מתבן	מ"ר לראש	1.5	מתבן למגדל חדש בדיר חדש עד 200 מ"ר.
	מרכז מזון מקורה	מ"ר לראש	1.5	מרכז מזון למגדל חדש בדיר חדש עד 200 מ"ר.
עד 300 כבשים	מכון חליבה, חצר המתנה, מחסן, מ.שירות	מ"ר	365	
	מבנה מכון	מ"ר	110	לפי 48 עמדות
	חצר המתנה	מ"ר	150	לפי 100 ראש בקבוצה ו2 קבוצות במקביל

הענף	סוג המבנה הנדרש	יחידת מידה	שטח ליחידה	הערות כלליות
עד 300 כבשים	מחסן, שירותים, חדר חלב	מ"ר	105	
מ- 301 עד 1000 כבשים	מכון חליבה, חצר המתנה, מחסן, מ.שירות	מ"ר	485	
	מבנה מכון	מ"ר	130	לפי 60 עמדות
	חצר המתנה	מ"ר	225	לפי 150 ראש בקבוצה ושתי קבוצות במקביל
	מחסן, שירותים, חדר חלב	מ"ר	130	
צאן לחלב בשטחי מרעה	שטח שיכון - סככה וחצר	מ"ר לעז או כבשה בוגרת, לצפירה או שיה	3	מגדל חדש – 100 ראש לפחות סככות שיכון בגודל 450 מ"ר מעל 200 ראש – 900 מ"ר לכל היותר. במקרים מיוחדים, בהיקפי גידול גדולים משמעותית ובהתאמה להיקפי שטח המרעה, ניתן לשקול הגדלת סככות השיכון עד ל1,200 מ"ר.
	מתבן	מ"ר	200	
	מחסן	מ"ר	30	
	סככת כלים	מ"ר	80	
	מכון חליבה	מ"ר	150	
צאן לבשר				
צאן לבשר בשטח בנוי	שטח שיכון - סככה וחצר	מ"ר לעז או כבשה בוגרת, לצפירה או שיה	5	מגדל חדש - 100 ראש לפחות ועד 200 ראש לכל היותר. עד 300 ראש - גודל הסככות יחושב לפי מספר הראשים הקיים כפול 2. בין 300 ל-400 ראש - עד 3,000 מ"ר. מעל 400 ראש - לפי מספר הראשים בפועל, בתוספת 1,000 מ"ר.
	מתבן	מ"ר לראש	1	מתבן למגדל חדש בדיר חדש עד 200 מ"ר, לעדר קיים לפי מפתח של 1 מ"ר לראש.
	מרכז מזון מקורה	מ"ר לראש	1	מרכז מזון למגדל חדש בדיר חדש עד 200 מ"ר, לעדר קיים, לפי מפתח של עד 1 מ"ר לראש.
	מחסן ומשרד כולל שירותים	מקסימום - מ"ר	100	לפי 20 מ"ר מחסן + 30 מ"ר מבנה שירות לעדר עד 400 ראש. מעל זה תוספת של 5 מ"ר לכל 100 ראש.
	סככת כלים	מקסימום - מ"ר	150	סככת כלים-עד 80 מ"ר לעדר של עד 400 אמהות. מעבר לכך 10 מ"ר נוספים לכל 100 ראש.
צאן לבשר בשטח פתוח	שטח שיכון - סככה וחצר	מ"ר לעז או כבשה בוגרת, לצפירה או שיה	4	מגדל חדש - 100 ראש לפחות ועד 200 ראש לכל היותר. עד 300 ראש - גודל הסככות יחושב לפי מספר הראשים הקיים כפול 2.
	מתבן	מ"ר לראש	1	מתבן למגדל חדש בדיר חדש עד 200 מ"ר, לעדר קיים לפי מפתח של 1 מ"ר לראש.
	מחסן ומשרד כולל שירותים	מקסימום - מ"ר	30	
	סככת כלים	מקסימום - מ"ר	80	
צאן לבשר בשטחי מרעה	שטח שיכון - סככה וחצר	מ"ר לעז או כבשה בוגרת, לצפירה או שיה	3	מגדל חדש – 100 ראש לפחות סככות שיכון בגודל 450 מ"ר מעל 200 ראש – 900 מ"ר לכל היותר. במקרים מיוחדים, בהיקפי גידול גדולים משמעותית ובהתאמה להיקפי שטח המרעה, ניתן לשקול הגדלת סככות השיכון עד ל1,200 מ"ר.
	מתבן	מ"ר	200	
	מחסן	מ"ר	30	
	סככת כלים	מ"ר	80	
לול מטילות				יש להעדיף מיקום מחוץ לנחלות בשטח חקלאי מיוחד או מבני משק וכד'
6,000 מטילות	מבנה לול	מ"ר	700	

הענף	סוג המבנה הנדרש	יחידת מידה	שטח ליחידה	הערות כלליות
12,000 מטילות	מבנה לול	מ"ר	1,000	
20,000 מטילות	מבנה לול	מ"ר	1,200	
40,000 מטילות	מבנה לול	מ"ר	1,500	
6,000 מטילות חופש או אורגני	מבנה לול	מ"ר	1,000	
6,000 מטילות מעוף (ללא כלובים)	מבנה לול	מ"ר	700	
6,000 מעוף (3 קומות כלובים)	מבנה לול	מ"ר	500	
מבנה שרות לחווה		מקסימום - מ"ר	60	
מחסן		מקסימום - מ"ר	100	בלול מעל 12,000 מטילות יותר מחסן גדול יותר עד 150 מ"ר.
לול פטם (לרבות רביה ובתי אימון)		252 טון בלול "בסיסי" בגודל 1200 מ"ר	1,200	לייצור 1000 טון בשנה יש צורך ב-4 לולים בסיסיים, כ-5000 מ"ר נטו בסה"כ
במתחם לולי פטם	מבנה שרות לחווה	מקסימום - מ"ר	60	
	מחסן	מקסימום - מ"ר	100	בלול מעל 2000 טון יותר מחסן גדול יותר עד 250 מ"ר.
לול פרגיות כבדות, רביה כבדה, רביה קלה, הודים, הודים - בתי אימון, הודים - לול פיטום	מבנה	מקסימום - מ"ר	1,000	
	מבנה שרות לחווה	מקסימום - מ"ר	60	
	מחסן	מקסימום - מ"ר	100	בלול מעל 2000 טון יותר מחסן גדול יותר עד 250 מ"ר.
אורווה				
	שטח שיכון וטיפולים לסוס כולל מחסן כלים וציוד	מ"ר לסוס	35	למגדל מתחיל המחזיק עד 2-5 סוסים בלבד, שטח האורווה על כל מרכיביה לא יעלה על 200 מ"ר.
	מחסן, שירות, שרותים, מקלחות	מקסימום - מ"ר	100	
	שרות- תצוגה, וטרינר, תרופות	מקסימום - מ"ר	60	
	מתבן בגובה 4 חבילות	מקסימום - מ"ר	350	
	מתבן בגובה 3 חבילות	מקסימום - מ"ר	490	
כלבייה				
בהתאם לכרטיס המבנה				
מדגה				
שטח פתוח	מחסן כלים	מ"ר	20	
	סככת כלים וציוד	מ"ר	80	מפולשת. מחסן 20 מ"ר כחלק מהסככה.
שטחי גידול (בריכות)	לפי המלצת מדריך			
מדגה אינטנסיבי	בריכות מקורות ו/או מבנה מבוקר לגידול			בהתאם להיקף הגידול ובכפוף להמלצת אגף הדיג.